Атлас

география

10-11 классы

Моргунов

СОДЕРЖАНИЕ

ГЕОГРАФИЧЕСКАЯ КАРТИНА МИРА

Политическая карта мира . . . 2—3
Размещение населения мира . . . 4—5
Языковые семьи и народы мира . . . 6—7
Официальные языки стран мира . . . 8
Религии мира . . . 9
ВВП стран мира . . . 10
Структура экономики стран мира . . . 11
Минеральные ресурсы мира . . . 12—13
Добывающая промышленность мира . . . 14—15
Электроэнергетика мира . . . 16—17
Обрабатывающая промышленность мира . . . 18—19
Агроклиматические ресурсы мира . . . 20—21
Сельское хозяйство мира . . . 22—23
Международная торговля товарами . . . 24
Международная инвестиции . . . 25
Мировой туризм . . . 26—27
Мировой транспорт . . . 28—29
Трубопроводный транспорт . . . 30

МНОГОЛИКАЯ ПЛАНЕТА

Великобритания . . . 31
Франция . . . 32
Германия . . . 33
Италия . . . 34
Китай . . . 35
Япония . . . 36
Индия . . . 37
Юго-Западная Азия . . . 38
Африка . . . 39
Соединённые Штаты Америки . . . 40
Канада . . . 41
Южная Америка . . . 42
Австралия . . . 43
Россия в мире . . . 44

ГЛОБАЛЬНЫЕ ПРОБЛЕМЫ ЧЕЛОВЕЧЕСТВА

Глобальная продовольственная проблема . . . 45
Экологические проблемы мира . . . 46—47
Интеграционные объединения . . . 48

География

10–11

классы

Атлас

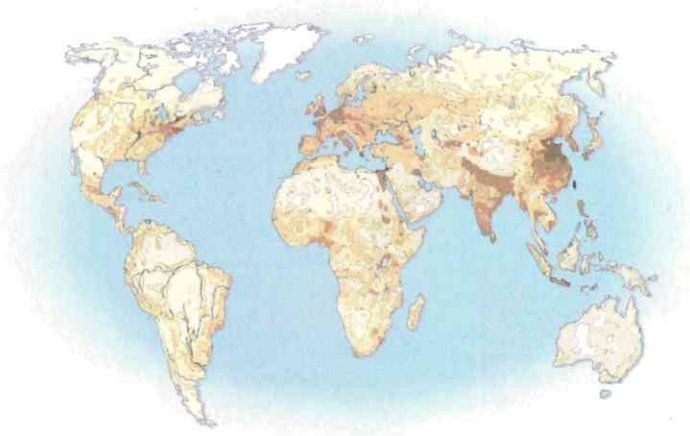

18-е издание, исправленное

Москва «Просвещение» 2023

ПОЛИТИЧЕСКАЯ КАРТА МИРА

Примечания:

1. Международно-правовой режим Антарктиды и других территорий, расположенных южнее 60° южной широты, регулируется Договором об Антарктике от 1 декабря 1959 г.
2. Будущее Западной Сахары подлежит урегулированию согласно соответствующим решениям ООН.
3. Майотта фактически является территориальной единицей Франции. Генеральная Ассамблея ООН признаёт права Союза Коморских Островов на остров Майотта (Маоре).
4. Фолклендские (Мальвинские) Острова — спорная между Аргентиной и Великобританией территория, находятся под административным управлением Великобритании.
5. Британская Территория в Индийском Океане создана вопреки решениям Генеральной Ассамблеи ООН.
6. Территории Палестины (Западный берег реки Иордан и сектор Газа) оккупированы Израилем в 1967 г. В настоящее время в рамках мирного урегулирования на Ближнем Востоке идёт процесс формирования государства Палестина.

КАРТЕ ОБОЗНАЧЕНЫ ГОСУДАРСТВА И ТЕРРИТОРИИ

И Я (Азия)

Катар
Объединённые Арабские Эмираты
Корейская Народно-Демократическая Республика
Республика Корея
Бутан
24 Бангладеш
25 Камбоджа
26 Малайзия
27 Бруней

АФРИКА

28 Тунис
29 Гамбия
30 Гвинея-Бисау
31 Гвинея
32 Сьерра-Леоне
33 Либерия
34 Кот-д'Ивуар
35 Буркина-Фасо
36 Гана
37 Того
38 Бенин
39 Экваториальная Гвинея
40 Центрально-африканская Республика
41 Эритрея
42 Джибути
43 Руанда
44 Бурунди
45 Замбия
46 Малави
47 Зимбабве
48 Эсватини
49 Лесото

АМЕРИКА

50 Гаити
51 Доминиканская Республика
52 Белиз
53 Гватемала
54 Гондурас
55 Сальвадор
56 Никарагуа
57 Коста-Рика
58 Панама
59 Суринам
60 Гвиана (Фр.)
61 Уругвай

РАЗМЕЩЕНИЕ НАСЕЛЕНИЯ МИРА

Масштаб 1:83 000 000

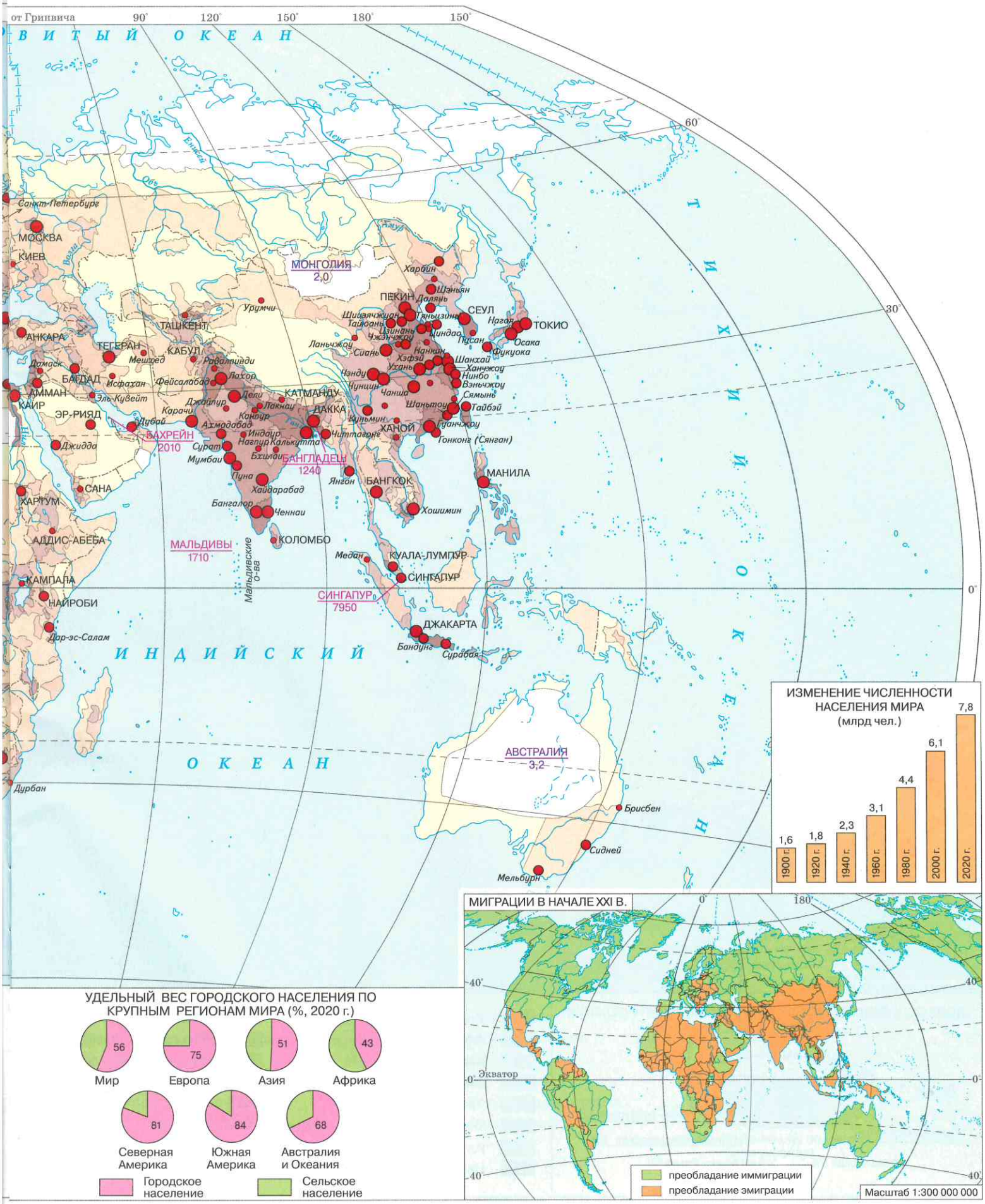
от Гринвича
90°
120°
150°
180°
150°
60°
30°
0°
ВИТЫЙ ОКЕАН
ТИХИЙ ОКЕАН
ИНДИЙСКИЙ ОКЕАН
Санкт-Петербург
МОСКВА
КИЕВ
Волга
Енисей
Лена
Обь
Амур
МОНГОЛИЯ
2,0
Харбин
Шэньян
ПЕКИН
Далянь
СЕУЛ
Нагоя
ТОКИО
Осака
Фукуока
Пусан
Шиязячжуан
Тайюань
Тяньцзинь
Цзинань
Чжэнчжоу
Циндао
Ланьчжоу
Сиань
Нанкин
Хэфэй
Шанхай
Ухань
Ханчжоу
Нинбо
Вэньчжоу
Чэнду
Чунцин
Чанша
Сямынь
Шаньтоу
Тайбэй
Гуанчжоу
Гонконг (Сянган)
Кунмин
ХАНОЙ
Читтагонг
Янгон
БАНГКОК
Хошимин
МАНИЛА
Медан
КУАЛА-ЛУМПУР
СИНГАПУР
СИНГАПУР
7950
ДЖАКАРТА
Бандунг
Сурабая
Урумчи
ТАШКЕНТ
АНКАРА
ТЕГЕРАН
Мешхед
КАБУЛ
Равалпинди
Лахор
Фейсалабад
Дамаск
БАГДАД
Исфахан
АММАН
Эль-Кувейт
КАИР
ЭР-РИЯД
Дубай
Джидда
БАХРЕЙН
2010
Карачи
Джайпур
Дели
Лакнау
Канпур
КАТМАНДУ
ДАККА
Ахмадабад
Индаур
Нагпур
Калькутта
Сурат
Мумбаи
Бхилаи
БАНГЛАДЕШ
1240
Пуна
Хайдарабад
Бангалор
Ченнаи
КОЛОМБО
МАЛЬДИВЫ
1710
Мальдивские о-ва
САНА
ХАРТУМ
АДДИС-АБЕБА
КАМПАЛА
НАЙРОБИ
Дар-эс-Салам
Дурбан
АВСТРАЛИЯ
3,2
Брисбен
Сидней
Мельбурн
ИЗМЕНЕНИЕ ЧИСЛЕННОСТИ НАСЕЛЕНИЯ МИРА (млрд чел.)
1,6
1,8
2,3
3,1
4,4
6,1
7,8
1900 г.
1920 г.
1940 г.
1960 г.
1980 г.
2000 г.
2020 г.
МИГРАЦИИ В НАЧАЛЕ XXI В.
0°
180°
40°
Экватор
преобладание иммиграции
преобладание эмиграции
Масштаб 1:300 000 000
УДЕЛЬНЫЙ ВЕС ГОРОДСКОГО НАСЕЛЕНИЯ ПО КРУПНЫМ РЕГИОНАМ МИРА (%, 2020 г.)
56
Мир
75
Европа
51
Азия
43
Африка
81
Северная Америка
84
Южная Америка
68
Австралия и Океания
Городское население
Сельское население

ЯЗЫКОВЫЕ СЕМЬИ И НАРОДЫ МИРА

Масштаб 1:83 000 000

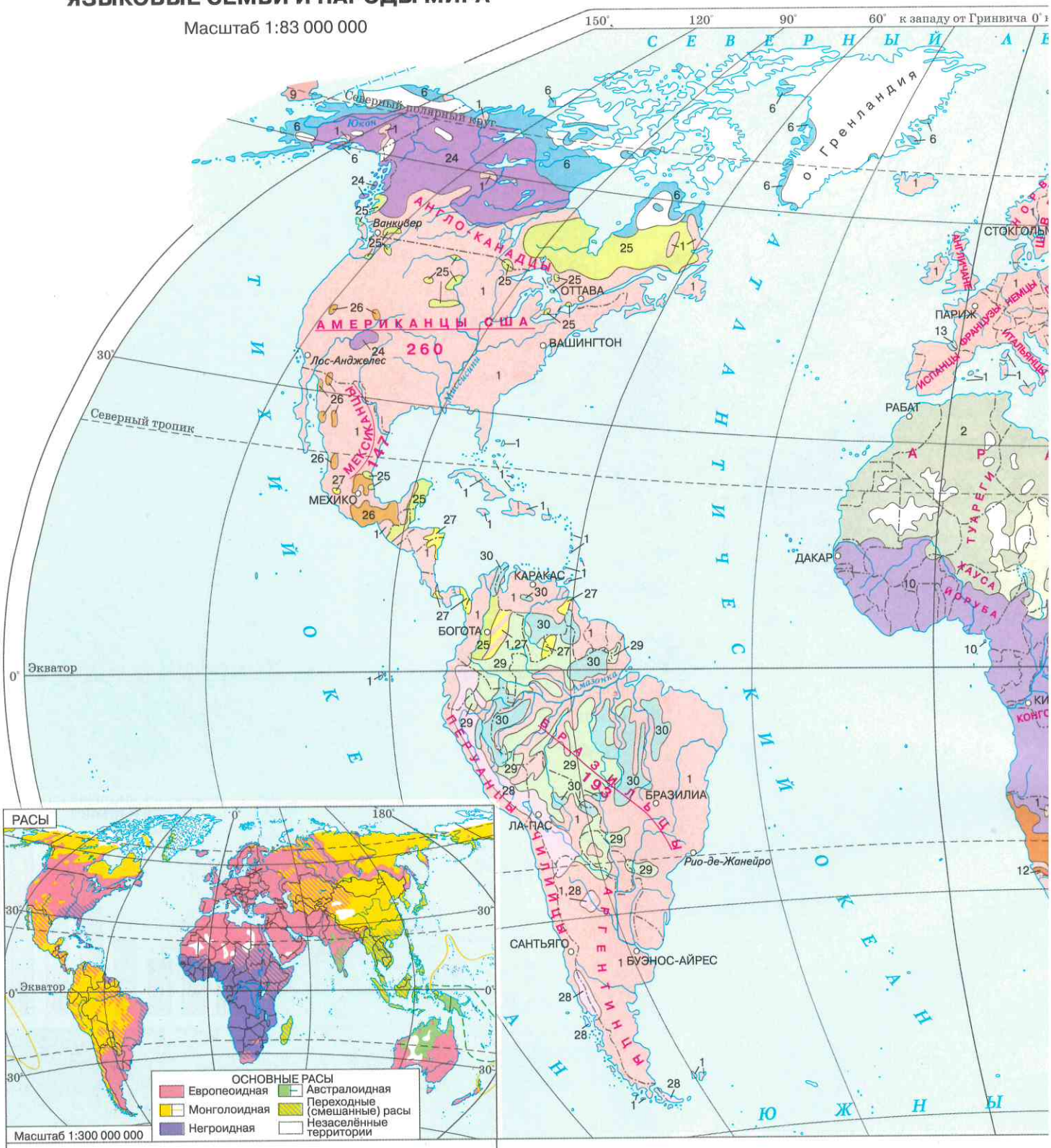

ДОЛЯ ОСНОВНЫХ ЯЗЫКОВЫХ СЕМЕЙ В МИРОВОМ НАСЕЛЕНИИ

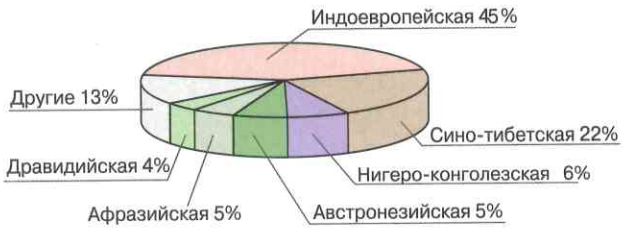

1. Индоевропейская семья
2. Афразийская семья
3. Картвельская семья
4. Дравидийская семья
5. Уральская семья
6. Эскимосско-алеутская семья
7. Алтайская семья
8. Нивхи
9. Чукотско-камчатская
10. Нигеро-конголезская
11. Нило-сахарская семь
12. Койсанская семья
13. Баски
14. Буриши
15. Северокавказская се
16. Кеты

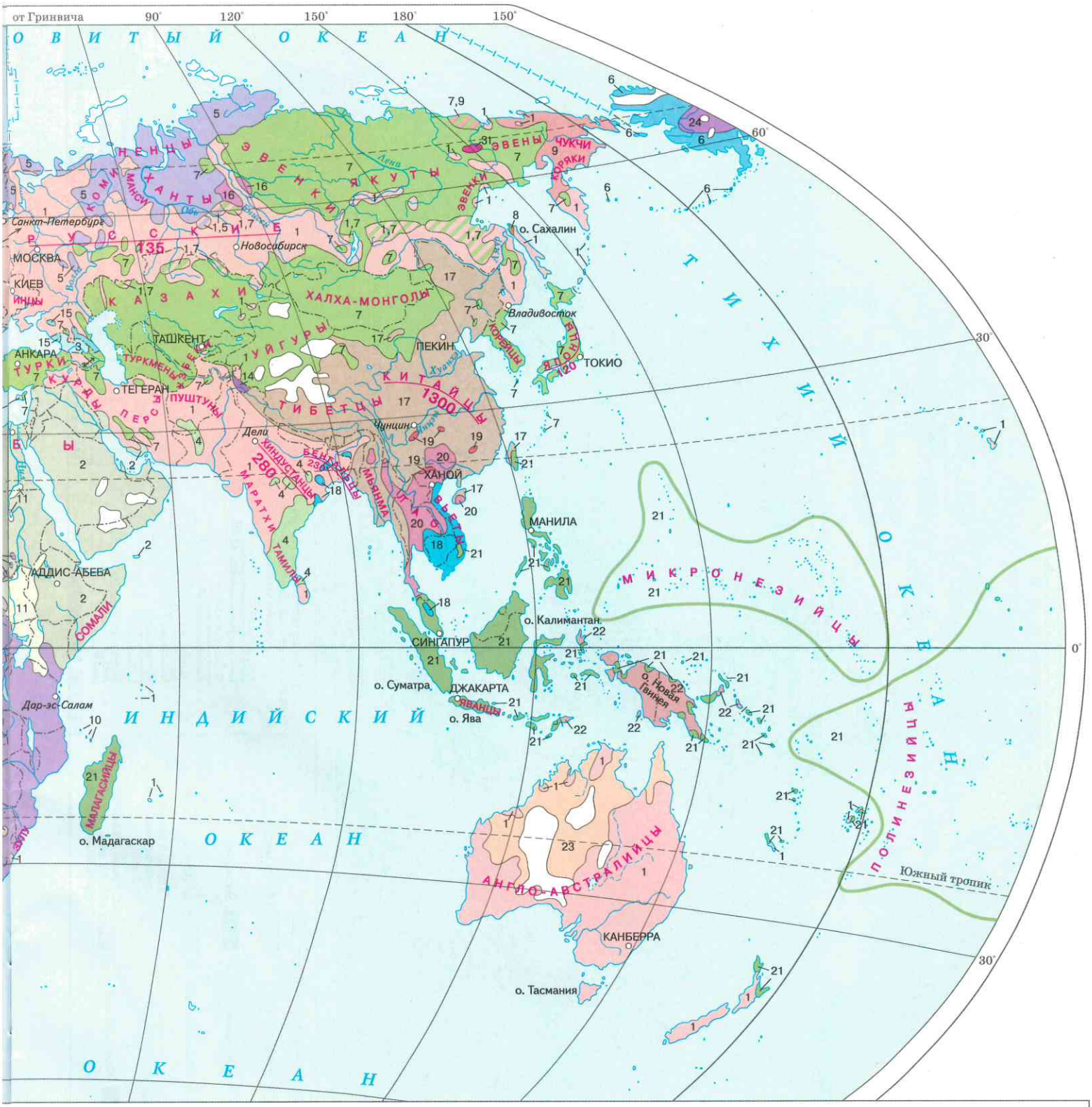

17	Сино-тибетская семья	25	Североамериндская семья		Территории с населением смешанного национального состава
18	Австроазиатская семья	26	Центральноамериндская семья		Незаселённые территории
19	Семья мяо-яо	27	Семья чибча-паэс		
20	Паратайская семья	28	Андская семья	ЯКУТЫ	Народы
21	Австронезийская семья	29	Экваториально-туканоанская семья	БРАЗИЛЬЦЫ 193	Крупнейшие по численности народы (млн человек)
22	Папуасские семьи	30	Же-пано-карибская семья		
23	Австралийские семьи	31	Юкагиры		
24	Семья на-дене				

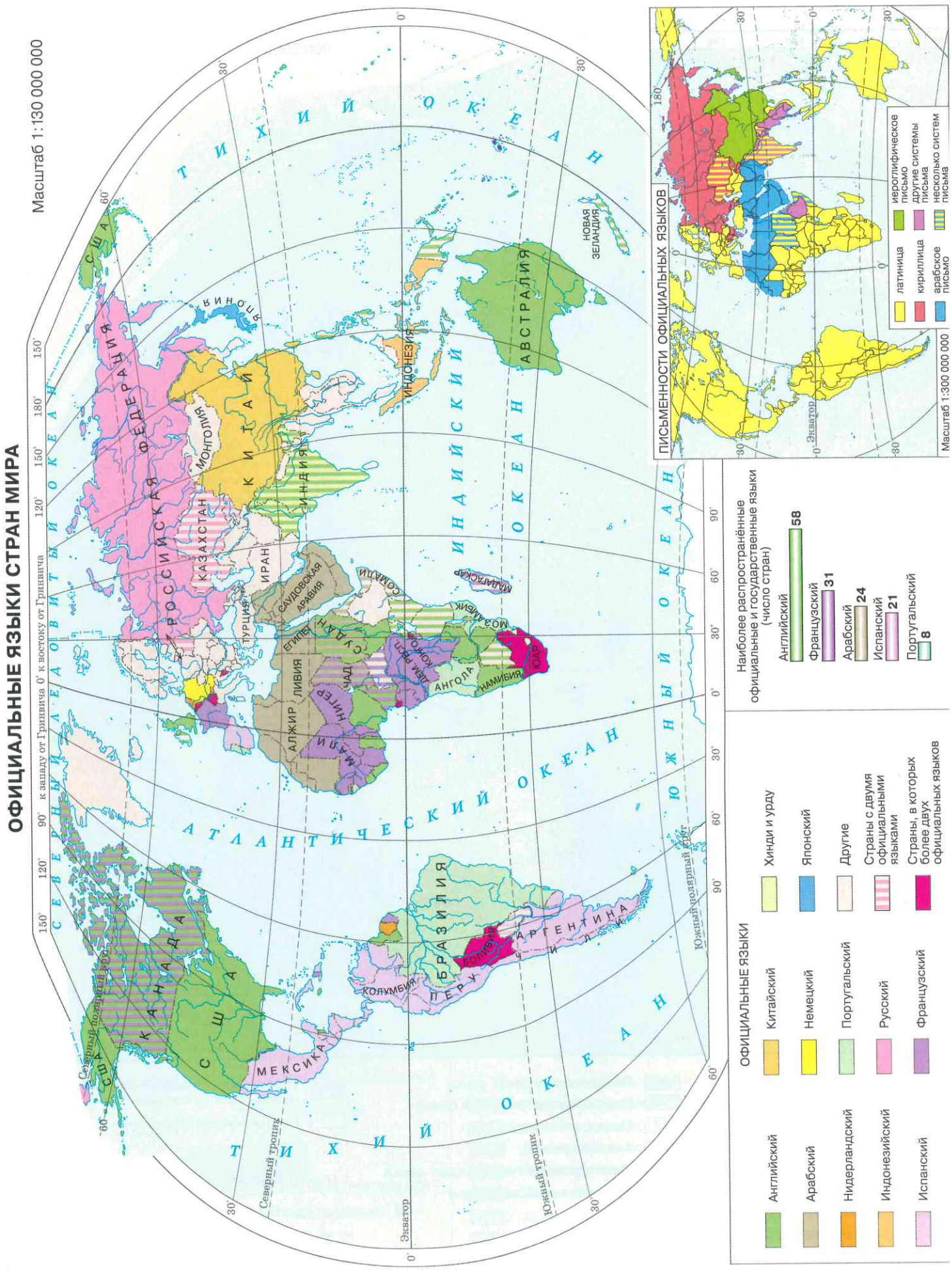
ОФИЦИАЛЬНЫЕ ЯЗЫКИ СТРАН МИРА
Масштаб 1:130 000 000
к западу от Гринвича 0° к востоку от Гринвича
ТИХИЙ ОКЕАН
АТЛАНТИЧЕСКИЙ ОКЕАН
ИНДИЙСКИЙ ОКЕАН
СЕВЕРНЫЙ ЛЕДОВИТЫЙ ОКЕАН
ЮЖНЫЙ ОКЕАН
РОССИЙСКАЯ ФЕДЕРАЦИЯ
КАЗАХСТАН
МОНГОЛИЯ
КИТАЙ
ИНДИЯ
ИРАН
ТУРЦИЯ
САУДОВСКАЯ АРАВИЯ
ЕГИПЕТ
ЛИВИЯ
АЛЖИР
ЧАД
НИГЕР
МАЛИ
СУДАН
ЭФИОПИЯ
СОМАЛИ
КЕНИЯ
УГАНДА
ДЕМ. РЕСП. КОНГО
АНГОЛА
МОЗАМБИК
МАДАГАСКАР
НАМИБИЯ
ЮАР
ИНДОНЕЗИЯ
АВСТРАЛИЯ
НОВАЯ ЗЕЛАНДИЯ
США
КАНАДА
МЕКСИКА
КОЛУМБИЯ
БРАЗИЛИЯ
ПЕРУ
БОЛИВИЯ
АРГЕНТИНА
ЧИЛИ
Северный полярный круг
Южный полярный круг
Северный тропик
Южный тропик
Экватор
ПИСЬМЕННОСТИ ОФИЦИАЛЬНЫХ ЯЗЫКОВ
Масштаб 1:300 000 000
латиница
кириллица
арабское письмо
иероглифическое письмо
другие системы письма
несколько систем письма
Наиболее распространённые официальные и государственные языки (число стран)
Английский 58
Французский 31
Арабский 24
Испанский 21
Португальский 8
ОФИЦИАЛЬНЫЕ ЯЗЫКИ
Английский
Арабский
Нидерландский
Индонезийский
Испанский
Китайский
Немецкий
Португальский
Русский
Французский
Хинди и урду
Японский
Другие
Страны с двумя официальными языками
Страны, в которых более двух официальных языков

РЕЛИГИИ МИРА

Масштаб 1:130 000 000

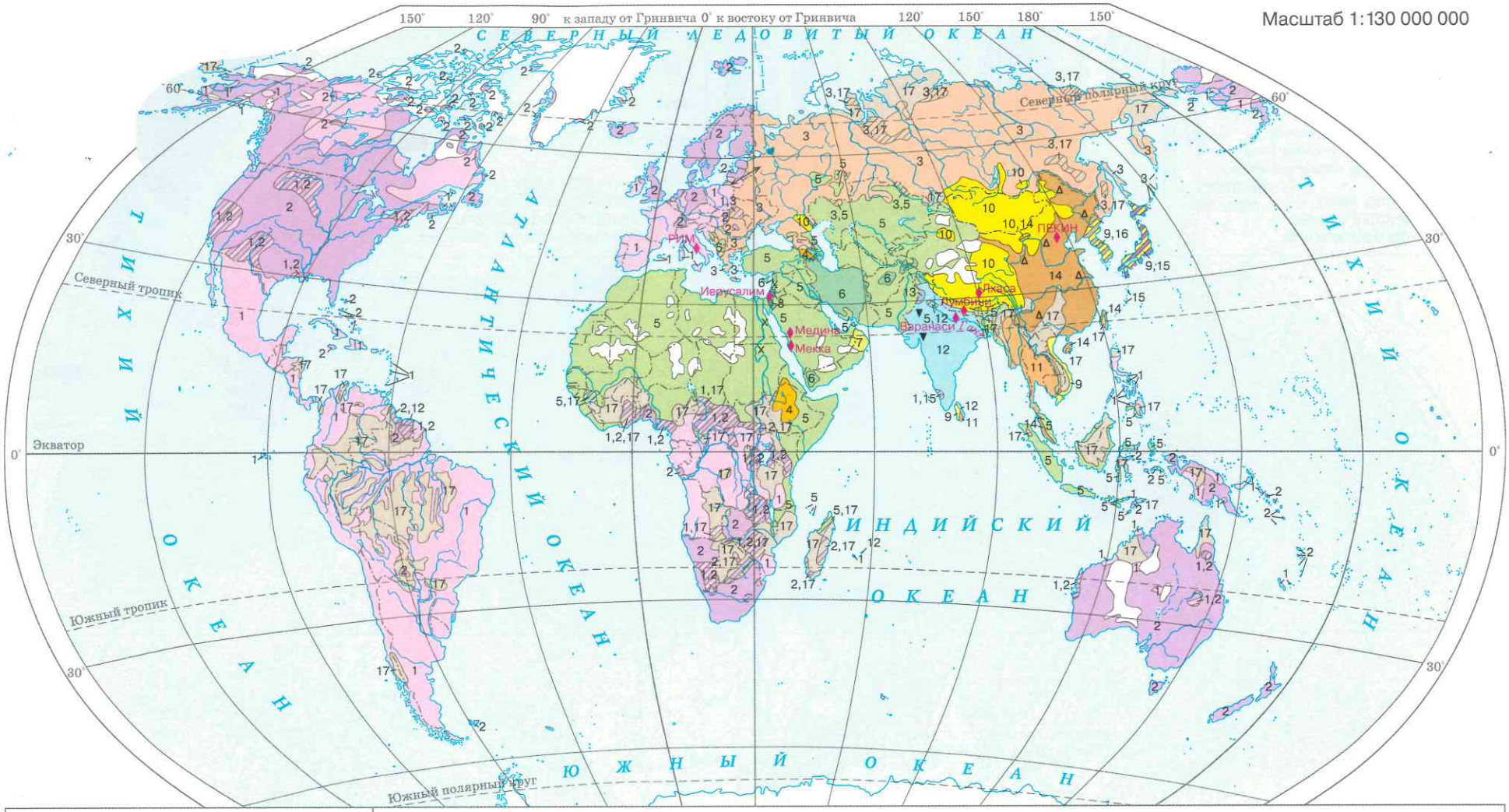

РАСПРЕДЕЛЕНИЕ ЧИСЛЕННОСТИ ВЕРУЮЩИХ ПО ОСНОВНЫМ РЕЛИГИЯМ

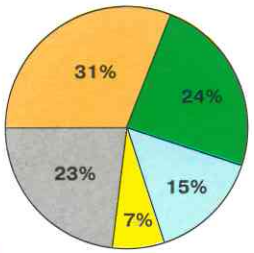

ХРИСТИАНЕ

- 1 Католики
- 2 Протестанты
- 3 Православные
- 4 × Монофизиты

МУСУЛЬМАНЕ

- 5 Сунниты
- 6 Шииты
- 7 Ибадиты
- 8 ИУДАИСТЫ

БУДДИСТЫ

- 9 Δ Махаянисты
- 10 Ламаисты
- 11 Тхеравадины
- 12 ИНДУИСТЫ
- 13 СИКХИ
- ▼ ДЖАЙНЫ
- 14 КОНФУЦИАНЦЫ
- 15 СИНТОИСТЫ
- 16 ПРИВЕРЖЕНЦЫ МЕСТНЫХ КОРЕЙСКИХ ВЕРОВАНИЙ
- 17 ПРИВЕРЖЕНЦЫ МЕСТНЫХ ТРАДИЦИОННЫХ ВЕРОВАНИЙ
- Население с примерно равным соотношением последователей двух основных верований
- Незаселённые территории

♦ СВЯЩЕННЫЕ МЕСТА

РИМ – католиков

Иерусалим – христиан, мусульман и иудаистов

Мекка и Медина – мусульман

Варанаси и Ганг – индуистов

Лумбини – буддистов

ПЕКИН – даосистов

Лхаса – ламаистов

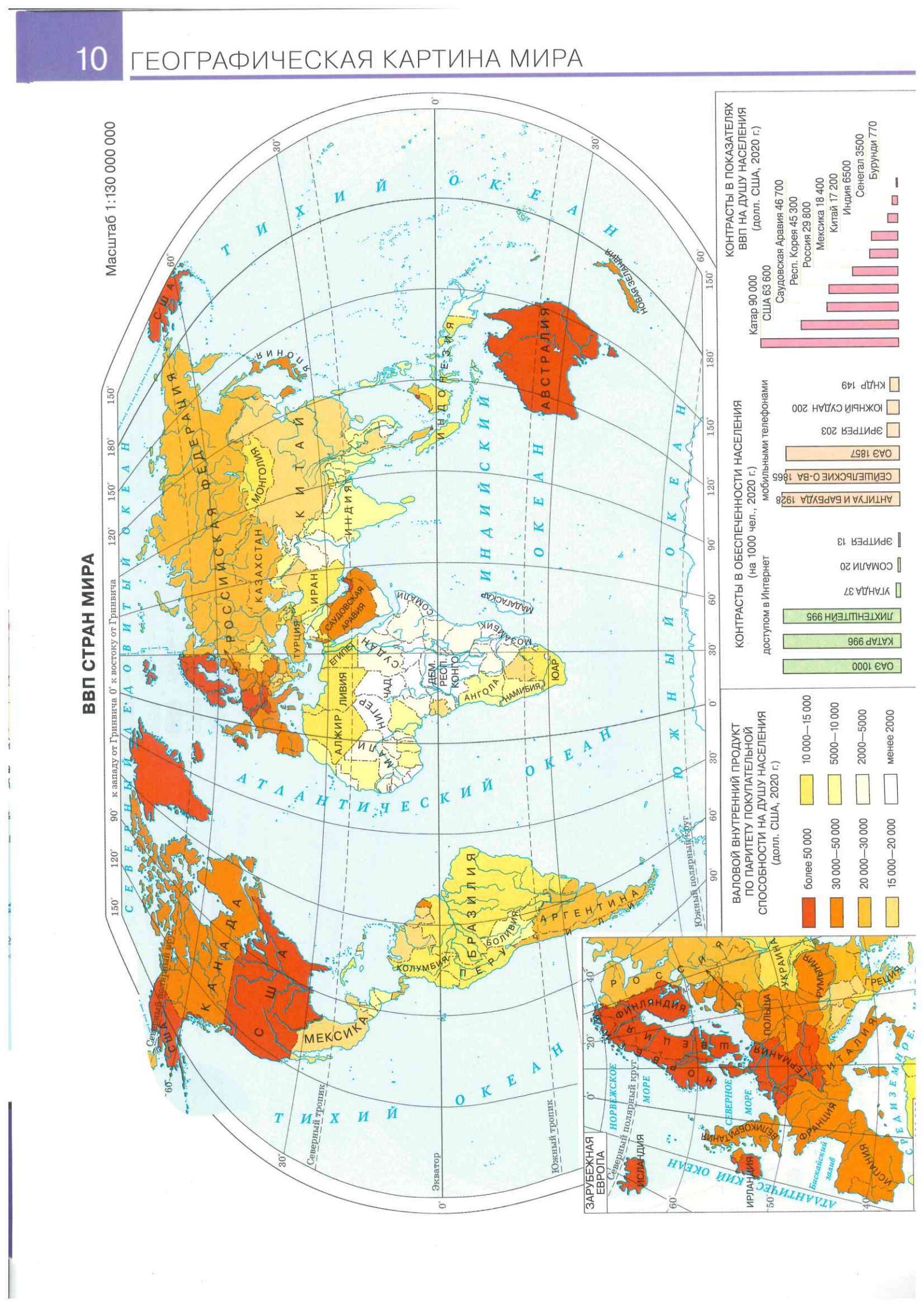
ВВП СТРАН МИРА
Масштаб 1:130 000 000
СЕВЕРНЫЙ ЛЕДОВИТЫЙ ОКЕАН
ТИХИЙ ОКЕАН
АТЛАНТИЧЕСКИЙ ОКЕАН
ИНДИЙСКИЙ ОКЕАН
ЮЖНЫЙ ОКЕАН
РОССИЙСКАЯ ФЕДЕРАЦИЯ
КАЗАХСТАН
МОНГОЛИЯ
КИТАЙ
ИНДИЯ
ИРАН
ТУРЦИЯ
САУДОВСКАЯ АРАВИЯ
ЯПОНИЯ
ИНДОНЕЗИЯ
НОВАЯ ЗЕЛАНДИЯ
АВСТРАЛИЯ
США
КАНАДА
МЕКСИКА
КОЛУМБИЯ
БРАЗИЛИЯ
БОЛИВИЯ
ПЕРУ
АРГЕНТИНА
ЧИЛИ
ЕГИПЕТ
ЛИВИЯ
АЛЖИР
НИГЕР
ЧАД
СУДАН
ДЕМ. РЕСП. КОНГО
АНГОЛА
НАМИБИЯ
ЮАР
МАДАГАСКАР
МОЗАМБИК
СОМАЛИ
Экватор
Северный тропик
Южный тропик
Северный полярный круг
Южный полярный круг
ЗАРУБЕЖНАЯ ЕВРОПА
ИСЛАНДИЯ
НОРВЕГИЯ
ФИНЛЯНДИЯ
ШВЕЦИЯ
РОССИЯ
ПОЛЬША
УКРАИНА
РУМЫНИЯ
ГРЕЦИЯ
ГЕРМАНИЯ
ИТАЛИЯ
ФРАНЦИЯ
ИСПАНИЯ
ИРЛАНДИЯ
НОРВЕЖСКОЕ МОРЕ
БЕЛОЕ МОРЕ
СЕВЕРНОЕ МОРЕ
БИСКАЙСКИЙ ЗАЛИВ
СРЕДИЗЕМНОЕ МОРЕ
АТЛАНТИЧЕСКИЙ ОКЕАН
ВАЛОВОЙ ВНУТРЕННИЙ ПРОДУКТ ПО ПАРИТЕТУ ПОКУПАТЕЛЬНОЙ СПОСОБНОСТИ НА ДУШУ НАСЕЛЕНИЯ (долл. США, 2020 г.)
более 50 000
30 000—50 000
20 000—30 000
15 000—20 000
10 000—15 000
5000—10 000
2000—5000
менее 2000
КОНТРАСТЫ В ОБЕСПЕЧЕННОСТИ НАСЕЛЕНИЯ (на 1000 чел., 2020 г.)
доступом в Интернет
ОАЭ 1000
КАТАР 996
ЛИХТЕНШТЕЙН 995
УГАНДА 37
СОМАЛИ 20
ЭРИТРЕЯ 13
мобильными телефонами
АНТИГУА И БАРБУДА 1928
СЕЙШЕЛЬСКИЕ О-ВА 1865
ОАЭ 1857
ЭРИТРЕЯ 203
ЮЖНЫЙ СУДАН 200
КНДР 149
КОНТРАСТЫ В ПОКАЗАТЕЛЯХ ВВП НА ДУШУ НАСЕЛЕНИЯ (долл. США, 2020 г.)
Катар 90 000
США 63 600
Саудовская Аравия 46 700
Респ. Корея 45 300
Россия 29 800
Мексика 18 400
Китай 17 200
Индия 6500
Сенегал 3500
Бурунди 770

СТРУКТУРА ЭКОНОМИКИ СТРАН МИРА

Масштаб 1:130 000 000

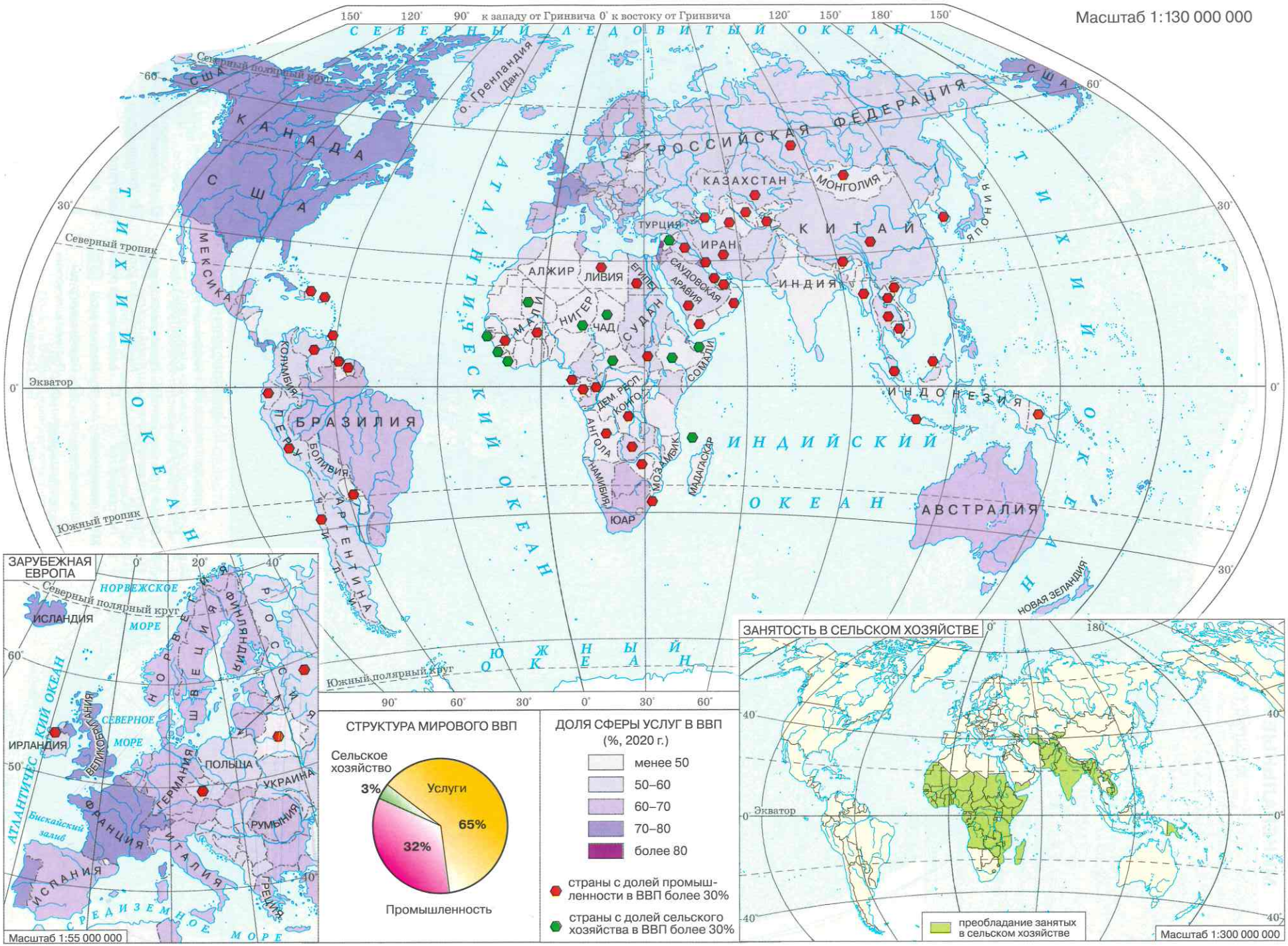

МИНЕРАЛЬНЫЕ РЕСУРСЫ МИРА

Масштаб 1:83 000 000

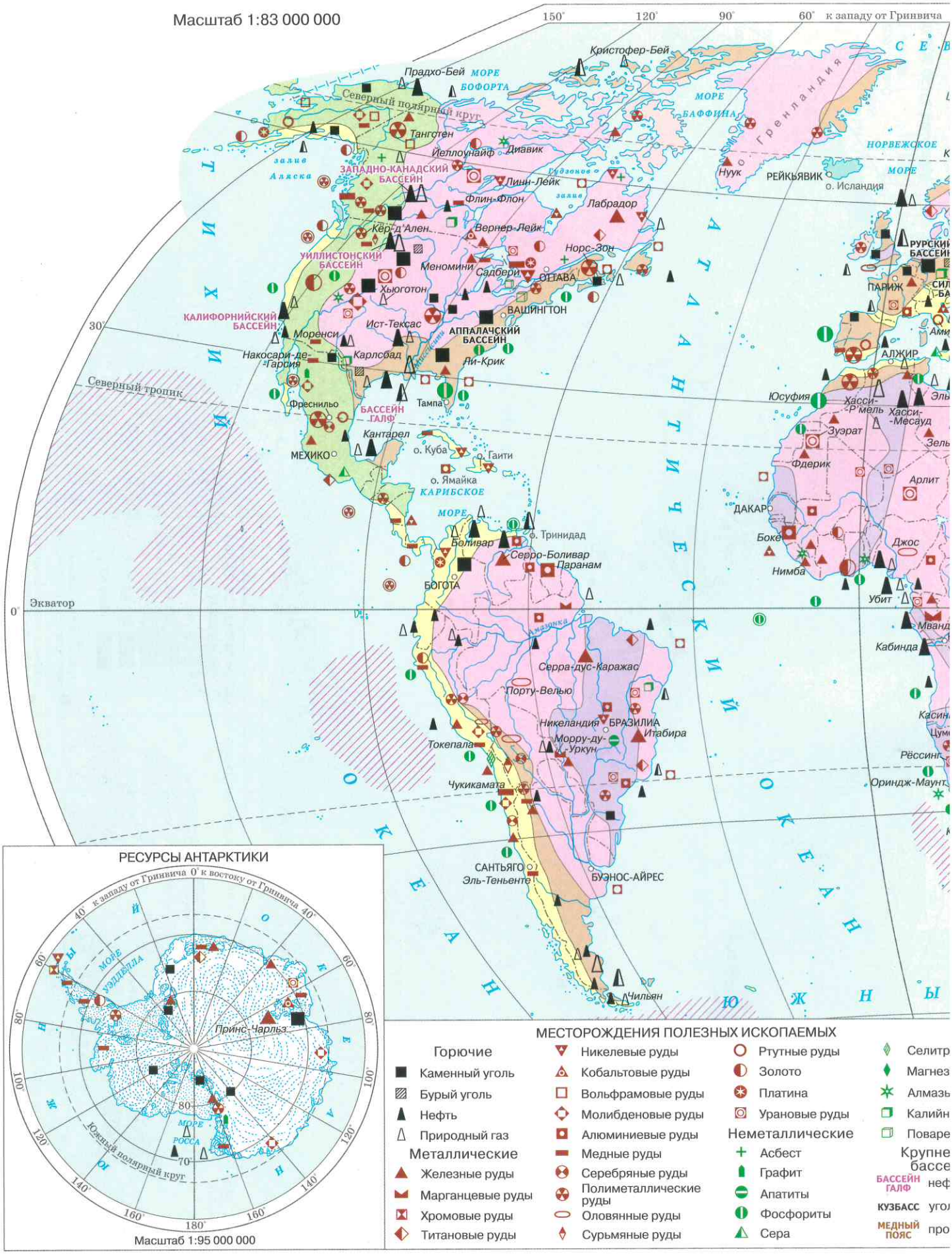

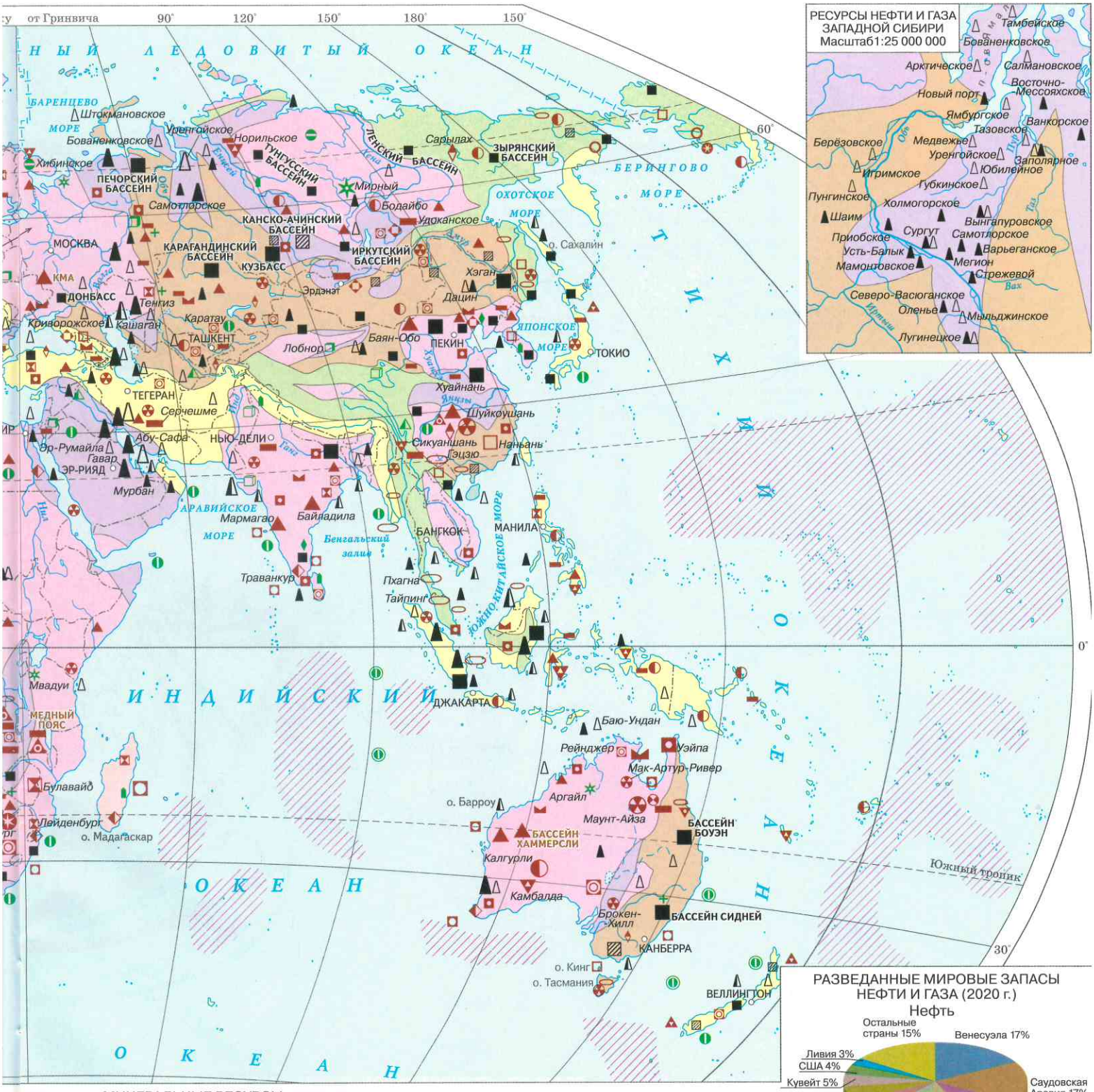

МИНЕРАЛЬНЫЕ РЕСУРСЫ ДНА МИРОВОГО ОКЕАНА

- Основные рудные поля железо-марганцевых конкреций
- Рудопроявления фосфоритов и кобальтовоносных железомарганцевых корок на подводных горах
- Нефтегазовые и газонефтяные месторождения
- Массивные полиметаллические сульфиды

Подводные россыпи

- магнетита и титаномагнетита
- ильменита, рутила, монацита, циркона

Примечание. Размер значков месторождений показывает объём запасов

ТЕКТОНИЧЕСКИЕ ОБЛАСТИ

Кора материкового типа

- Платформы и крупные платформенные массивы с доверхнепротерозойским фундаментом
- Области позднепротерозойской (байкальской) и кембрийской (раннекаледонской) складчатости
- Области палеозойской (каледонской и герцинской) складчатости
- Области мезозойской складчатости
- Области кайнозойской складчатости

Кора океанического типа

- Области с корой океанического типа, поднятой над уровнем моря

Криворожское Названия месторождений

РАЗВЕДАННЫЕ МИРОВЫЕ ЗАПАСЫ НЕФТИ И ГАЗА (2020 г.)

Нефть

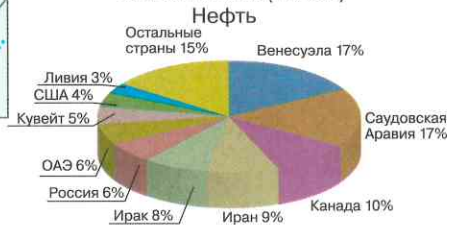

Газ

ДОБЫВАЮЩАЯ ПРОМЫШЛЕННОСТЬ МИРА

Масштаб 1:83 000 000

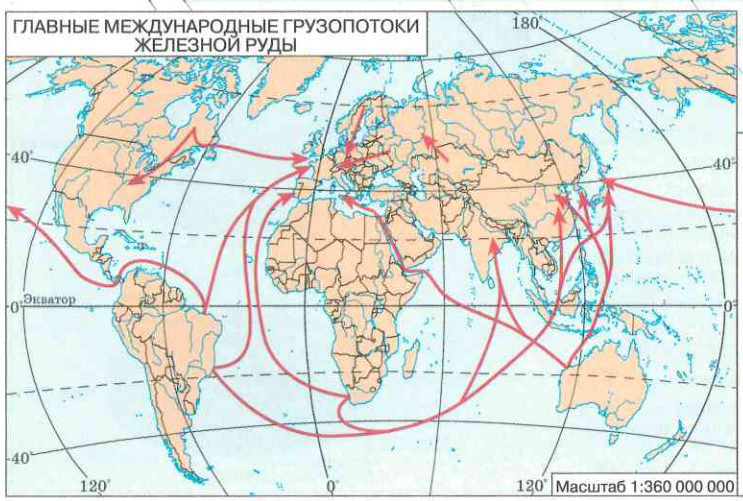

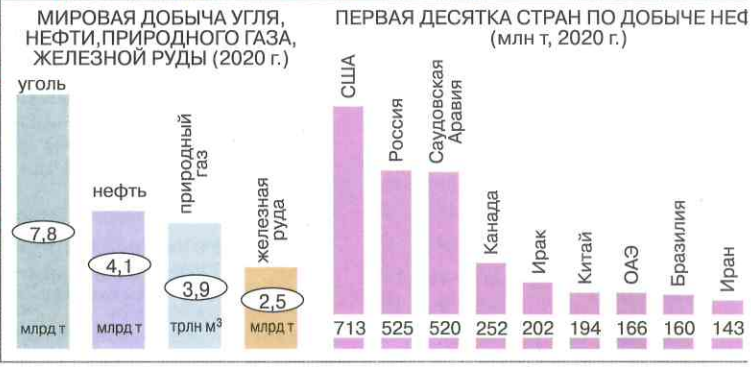

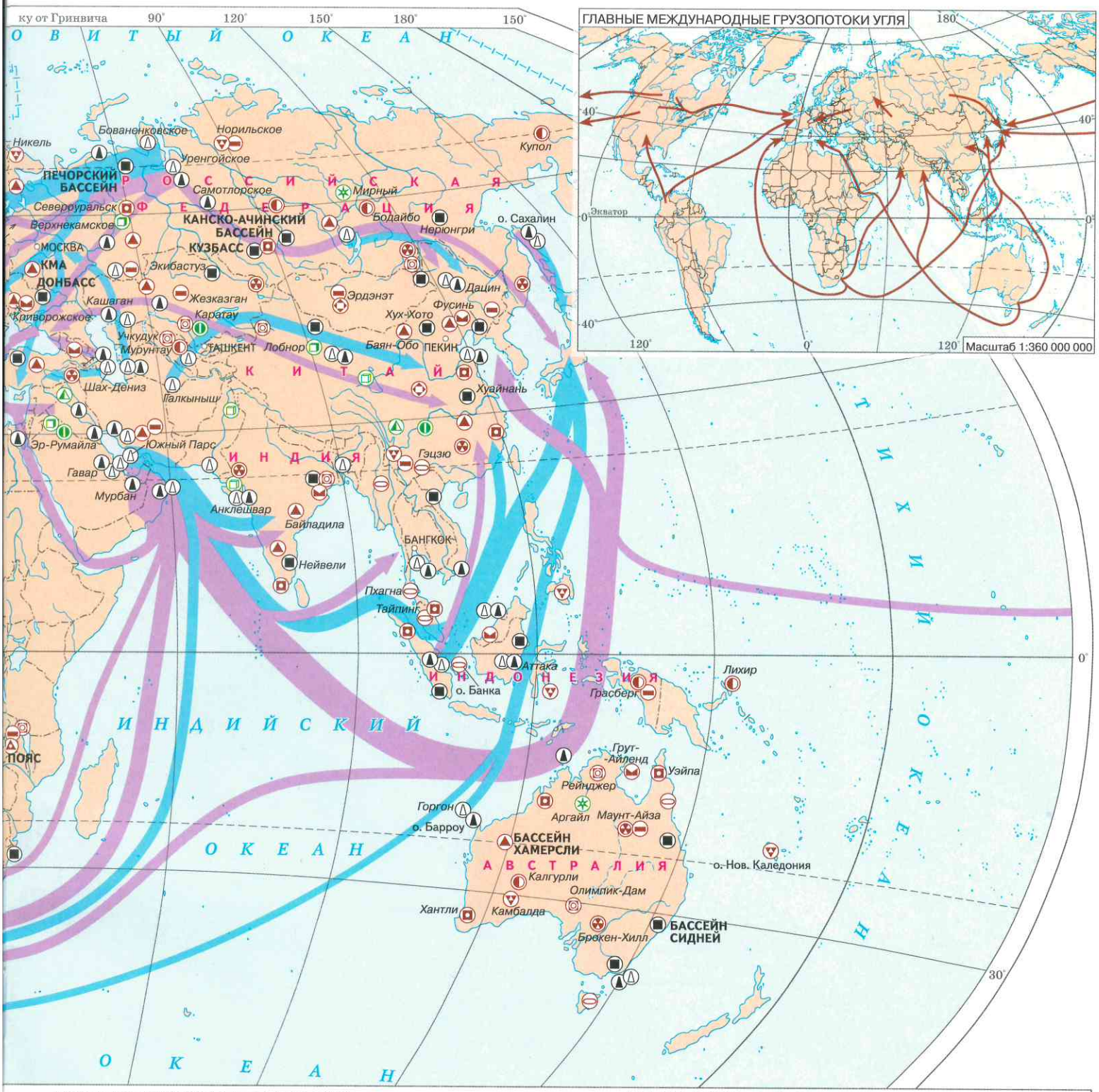
ГЛАВНЫЕ МЕЖДУНАРОДНЫЕ ГРУЗОПОТОКИ УГЛЯ
Масштаб 1:360 000 000
Экватор
ку от Гринвича
90°
120°
150°
180°
150°
О В И Т Ы Й О К Е А Н
Никель
Бованенковское
Норильское
Уренгойское
Купол
ПЕЧОРСКИЙ БАССЕЙН
Самотлорское
Мирный
Р О С С И Й С К А Я
Ф Е Д Е Р А Ц И Я
Северо-уральск
Верхнекамское
КАНСКО-АЧИНСКИЙ БАССЕЙН
Бодайбо
Нерюнгри
о. Сахалин
МОСКВА
КУЗБАСС
КМА
ДОНБАСС
Экибастуз
Кашаган
Жезказган
Эрдэнэт
Дацин
Криворожское
Каратау
Хух-Хото
Фусинь
Учкудук
Мурунтау
ТАШКЕНТ
Лобнор
Баян-Обо
ПЕКИН
К И Т А Й
Шах-Дениз
Галкыныш
Хуайнань
Эр-Румайла
Южный Парс
И Н Д И Я
Гэцзю
Гавар
Мурбан
Анклешвар
Байпадила
БАНГКОК
Нейвели
Пхагна
Тайпинг
Аттака
И Н Д О Н Е З И Я
о. Банка
Лихир
Грасберг
И Н Д И Й С К И Й
ПОЯС
Грут-Айленд
Уэйпа
Рейнджер
Аргайл
Маунт-Айза
Горгон
о. Барроу
БАССЕЙН ХАМЕРСЛИ
О К Е А Н
А В С Т Р А Л И Я
о. Нов. Каледония
Калгурли
Олимпик-Дам
Хантли
Камбалда
Брокен-Хилл
БАССЕЙН СИДНЕЙ
Т И Х О Е О К Е А Н
О К Е А Н
ПЕРВАЯ ДЕСЯТКА СТРАН ПО ДОБЫЧЕ ГАЗА
(млрд м³, 2020 г.)
США 914
Россия 638
Иран 250
Катар 194
Китай 171
Канада 165
Австралия 142
Норвегия 115
Саудовская Аравия 112
Алжир 81
ДОБЫЧА ПОЛЕЗНЫХ ИСКОПАЕМЫХ
горючих
угля
нефти
природного газа
металлических
железных руд
марганцевых руд
никелевых руд
кобальтовых руд
алюминиевых руд
медных руд
полиметаллических руд
оловянных руд
золота
урановых руд
молибденовых руд
неметаллических
серы
селитры
калийных солей
фосфоритов
алмазов
поваренной соли
Кашаган Названия месторождений
МЕЖДУНАРОДНЫЕ ГРУЗОПОТОКИ
нефти
газа
Крупнейшие
Крупные
Значительные
Примечание. Красным цветом подписаны страны-лидеры по добыче полезных ископаемых

ЭЛЕКТРОЭНЕРГЕТИКА МИРА

Масштаб 1:83 000 000

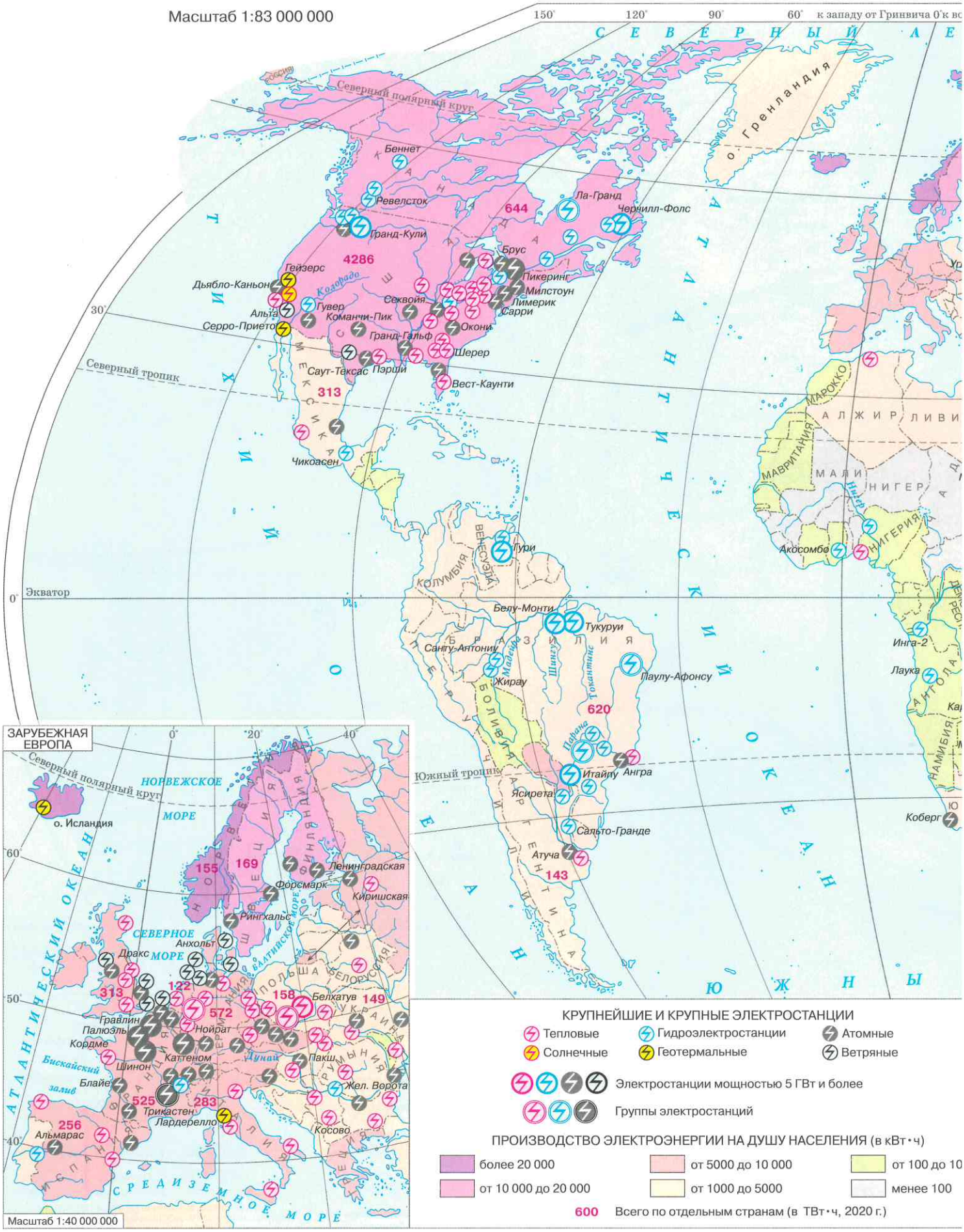

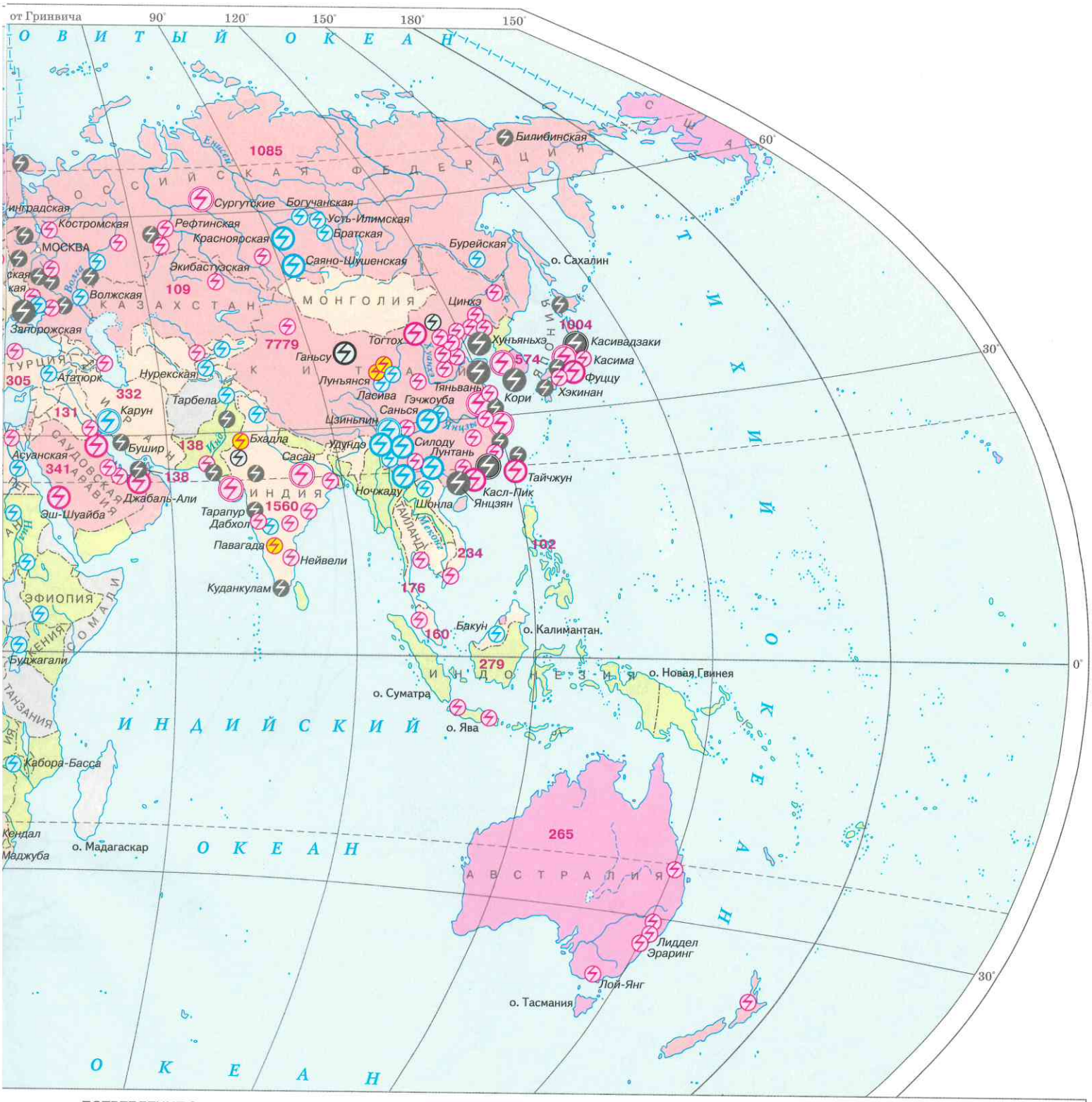

ПОТРЕБЛЕНИЕ ЭЛЕКТРОЭНЕРГИИ
(Мировое потребление 100%, 2020 г.

ДОЛЯ ВЕДУЩИХ СТРАН В МИРОВОМ ПРОИЗВОДСТВЕ ЭЛЕКТРОЭНЕРГИИ
(2020 г.)

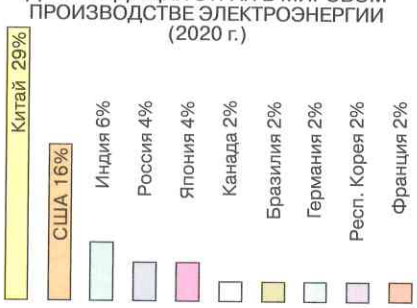

СТРУКТУРА МИРОВОГО ПРОИЗВОДСТВА ЭЛЕКТРОЭНЕРГИИ (%, 2020 г.)

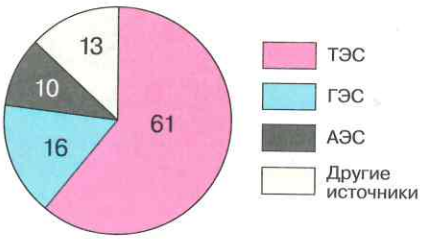

ОБРАБАТЫВАЮЩАЯ ПРОМЫШЛЕННОСТЬ МИРА

Масштаб 1:83 000 000

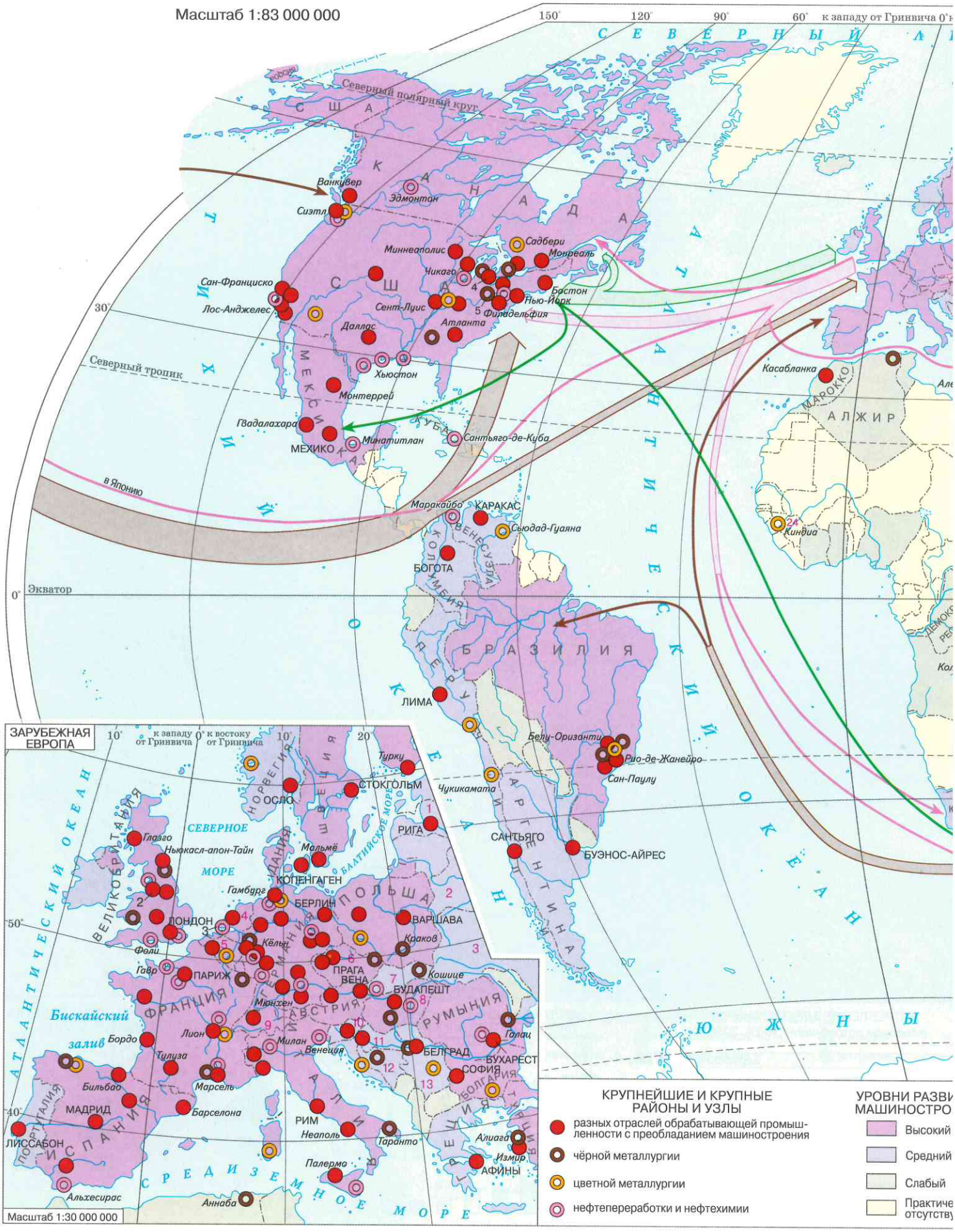

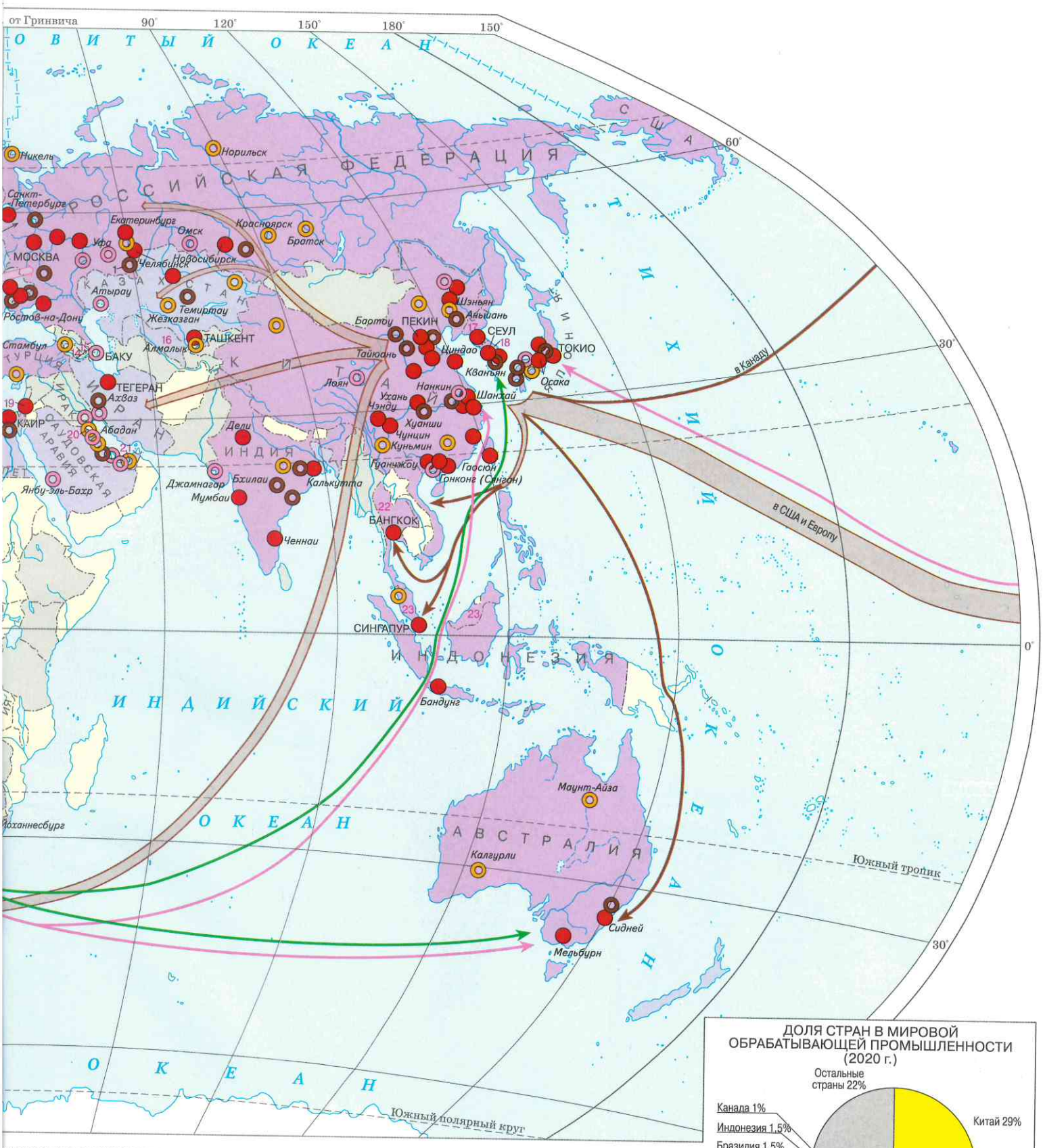

ЭКСПОРТ МАШИН И ОБОРУДОВАНИЯ

- из стран Западной Европы
- из США
- из стран Восточной Азии

Примечание. Толщина стрелок соответствует объёму экспорта

ЦИФРАМИ НА КАРТЕ ОБОЗНАЧЕНЫ:

Государства

ЕВРОПА
1 Латвия
2 Белоруссия
3 Украина
4 Нидерланды
5 Бельгия
6 Чехия
7 Словакия
8 Венгрия
9 Швейцария
10 Словения
11 Хорватия
12 Босния и Герцеговина
13 Сербия

АЗИЯ
14 Армения
15 Азербайджан
16 Узбекистан
17 КНДР
18 Респ. Корея
19 Израиль
20 Кувейт
21 ОАЭ
22 Таиланд
23 Малайзия

АФРИКА
24 Гвинея

Районы и узлы

1 Магнитогорск
2 Ливерпуль — Манчестер
3 Роттердам
4 Детройт
5 Питтсбург

ДОЛЯ СТРАН В МИРОВОЙ ОБРАБАТЫВАЮЩЕЙ ПРОМЫШЛЕННОСТИ (2020 г.)

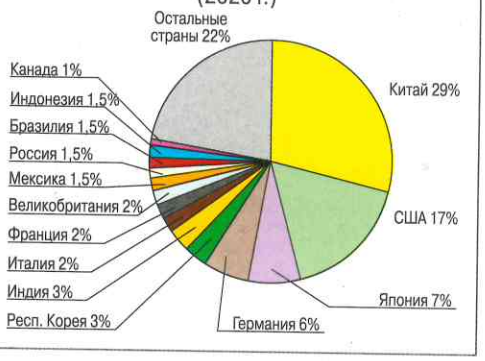

АГРОКЛИМАТИЧЕСКИЕ РЕСУРСЫ МИРА

Масштаб 1:83 000 000

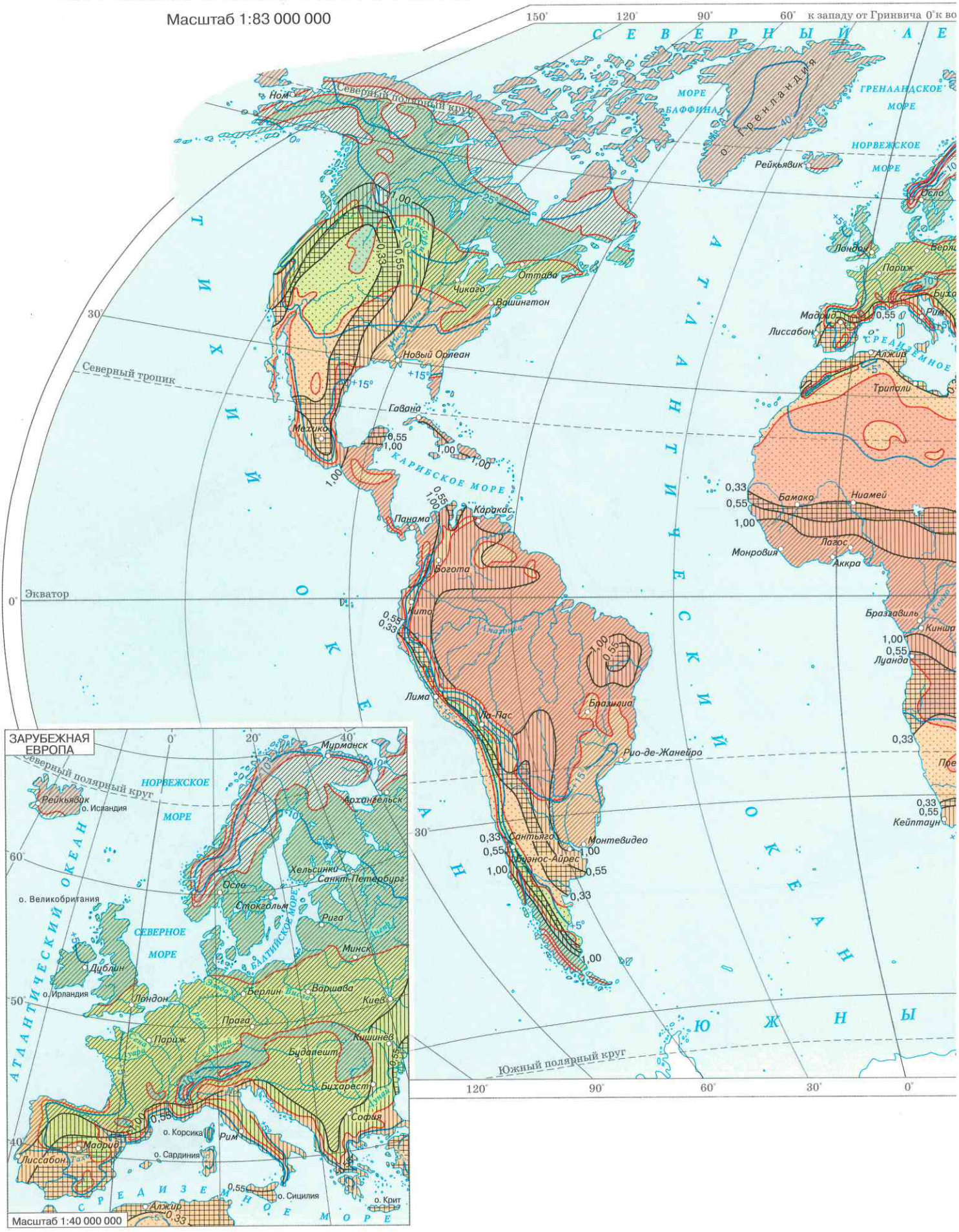

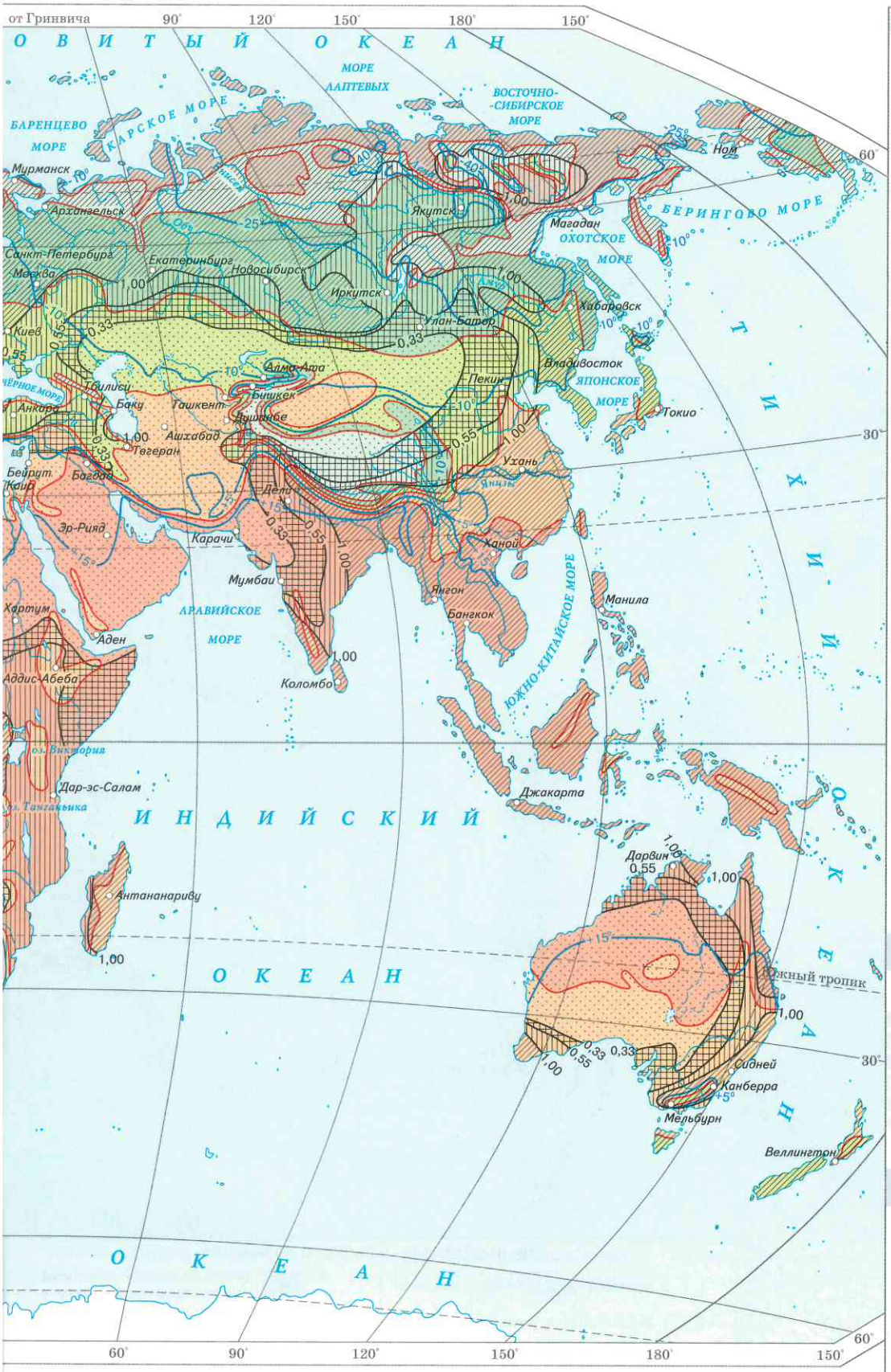

ОБЕСПЕЧЕННОСТЬ РАСТЕНИЙ ТЕПЛОМ

СУММА ТЕМПЕРАТУР ВОЗДУХА ЗА ПЕРИОД С ТЕМПЕРАТУРОЙ ВЫШЕ 10 °С	ХАРАКТЕРНЫЕ ДЛЯ ПОЯСОВ СЕЛЬСКОХОЗЯЙСТВЕННЫЕ КУЛЬТУРЫ
ХОЛОДНЫЙ ПОЯС	
Короткий период вегетации с летними заморозками	
менее 400	Овощеводство закрытого грунта
400—1000	Очаговое земледелие, малотребовательные к теплу овощные культуры — редис, шпинат, лук на перо, репа, ранний картофель
УМЕРЕННЫЙ ПОЯС	
ХОЛОДНО-УМЕРЕННЫЙ ПОДПОЯС	
Культуры с коротким вегетационным периодом	
1000—2200	Рожь, пшеница, зернобобовые, лён, картофель, плодовые, ягодники
УМЕРЕННЫЙ ПОДПОЯС	
Культуры со среднепродолжительным и длинным вегетационным периодом	
2200—4000	Поздние сорта зерновых, кукуруза на зерно, подсолнечник, сахарная свёкла, в южной части подпояса — рис, виноград
СУБТРОПИЧЕСКИЙ ПОЯС	
Теплолюбивые культуры с очень длинным вегетационным периодом	
4000—8000	Хлопчатник, кукуруза поздняя, оливки, цитрусовые, чай, табак, местами финиковая пальма и др.
ТРОПИЧЕСКИЙ ПОЯС	
Непрерывная вегетация растений в течение всего года (может прерываться сухим периодом). Сбор нескольких урожаев за год	
более 8000	Теплолюбивые многолетние и однолетние культуры с наиболее длительным периодом вегетации. Сахарный тростник, кофе, какао, хинное дерево, каучуконосы, масличная пальма и др.

Изолинии сумм температур воздуха выше 10 °С

ТИПЫ ЗИМЫ

по температуре самого холодного месяца в году (в градусах Цельсия)

Зима отсутствует	выше +15°
Тёплая	+15°... +5°
Мягкая	+5°... -10°
Холодная	-10°... -25°
Суровая	-25°... -40°
Очень суровая	ниже -40°

—-10°— Изотермы самого холодного месяца в году

ОБЕСПЕЧЕННОСТЬ РАСТЕНИЙ ВЛАГОЙ

ЗОНЫ УВЛАЖНЕНИЯ

ВЛАЖНАЯ — осадки превышают испаряемость или возможное испарение. Коэффициент увлажнения более 1,0

ЗАСУШЛИВАЯ — испаряемость превышает осадки
а) слабозасушливая
Коэффициент увлажнения 0,55 —1,0

б) засушливая
Коэффициент увлажнения 0,33 — 0,55

СУХАЯ — испаряемость значительно превышает осадки.
Коэффициент увлажнения менее 0,33

Примечание. Коэффициент увлажнения — отношение количества осадков к испаряемости за год

—0,33— Границы зон увлажнения

СЕЛЬСКОЕ ХОЗЯЙСТВО МИРА

Масштаб 1:83 000 000

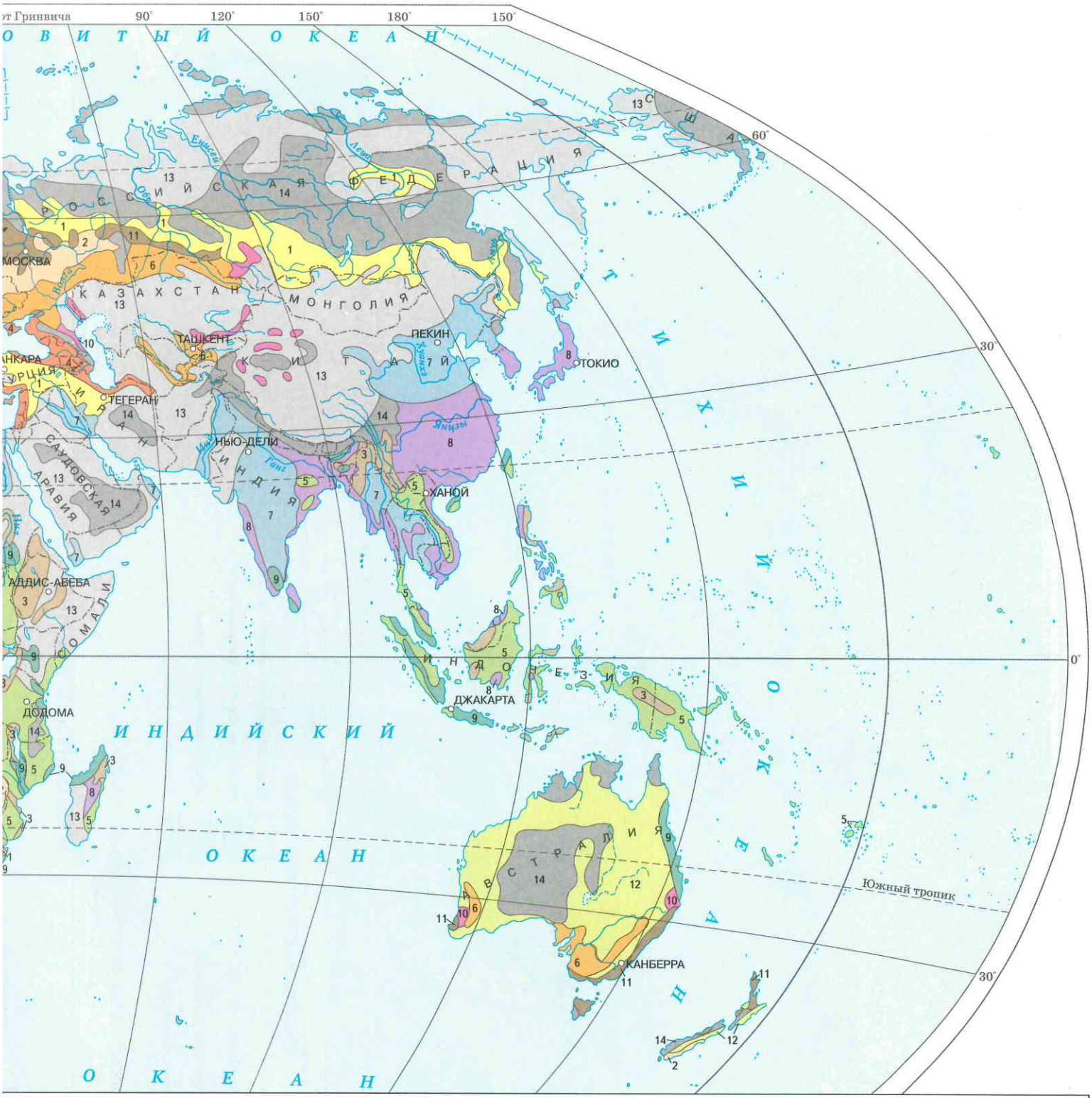

СТРАНЫ-ЛИДЕРЫ ПО СБОРУ ОТДЕЛЬНЫХ СЕЛЬСКОХОЗЯЙСТВЕННЫХ КУЛЬТУР (млн т, 2020 г.)

МИРОВОЙ СБОР ВАЖНЕЙШИХ ПРОДОВОЛЬСТВЕННЫХ КУЛЬТУР (млн т, 2020 г.)

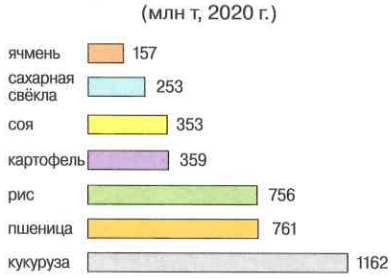

МИРОВОЕ ПОГОЛОВЬЕ СКОТА (млн голов, 2020 г.)

СТРУКТУРА ПОСЕВНЫХ ПЛОЩАДЕЙ ЗЕРНОВЫХ КУЛЬТУР (%, 2020 г.)

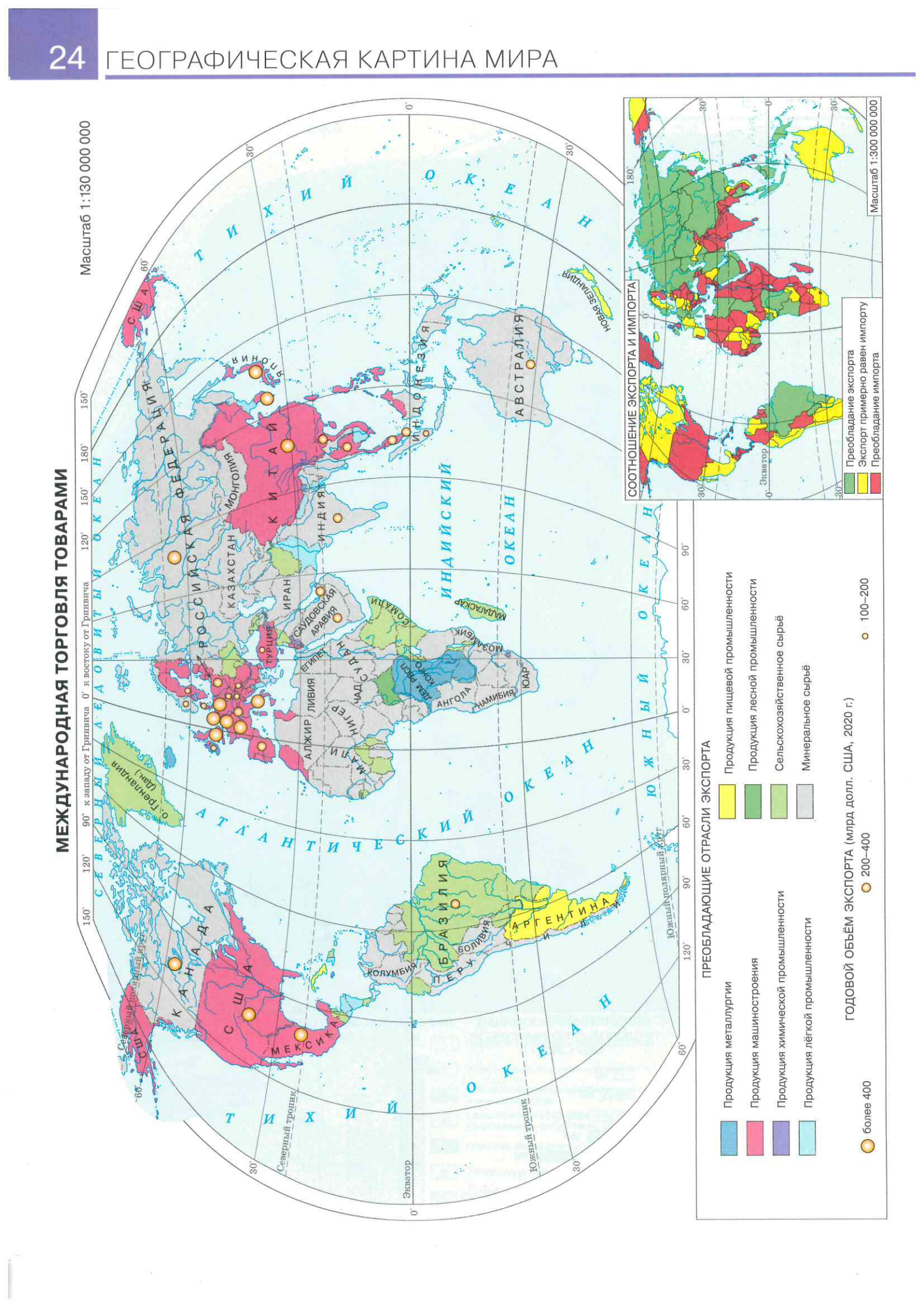
МЕЖДУНАРОДНАЯ ТОРГОВЛЯ ТОВАРАМИ
Масштаб 1:130 000 000
СЕВЕРНЫЙ ЛЕДОВИТЫЙ ОКЕАН
ТИХИЙ ОКЕАН
АТЛАНТИЧЕСКИЙ ОКЕАН
ИНДИЙСКИЙ ОКЕАН
ЮЖНЫЙ ОКЕАН
РОССИЙСКАЯ ФЕДЕРАЦИЯ
КАЗАХСТАН
МОНГОЛИЯ
КИТАЙ
ЯПОНИЯ
ИНДИЯ
ИРАН
САУДОВСКАЯ АРАВИЯ
ТУРЦИЯ
ЕГИПЕТ
ЛИВИЯ
АЛЖИР
МАЛИ
НИГЕР
ЧАД
СУДАН
СОМАЛИ
ЭФИОПИЯ
КЕНИЯ
ЗАИР
АНГОЛА
НАМИБИЯ
ЮАР
МОЗАМБИК
МАДАГАСКАР
ИНДОНЕЗИЯ
АВСТРАЛИЯ
НОВАЯ ЗЕЛАНДИЯ
США
КАНАДА
МЕКСИКА
КОЛУМБИЯ
ПЕРУ
БОЛИВИЯ
БРАЗИЛИЯ
АРГЕНТИНА
о. Рейнджана (Дан.)
Северный полярный круг
Южный полярный круг
Северный тропик
Южный тропик
Экватор
ПРЕОБЛАДАЮЩИЕ ОТРАСЛИ ЭКСПОРТА
Продукция металлургии
Продукция машиностроения
Продукция химической промышленности
Продукция лёгкой промышленности
Продукция пищевой промышленности
Продукция лесной промышленности
Сельскохозяйственное сырьё
Минеральное сырьё
ГОДОВОЙ ОБЪЁМ ЭКСПОРТА (млрд долл. США, 2020 г.)
более 400
200–400
100–200
СООТНОШЕНИЕ ЭКСПОРТА И ИМПОРТА
Преобладание экспорта
Экспорт примерно равен импорту
Преобладание импорта
Масштаб 1:300 000 000

МЕЖДУНАРОДНЫЕ ИНВЕСТИЦИИ

Масштаб 1:130 000 000

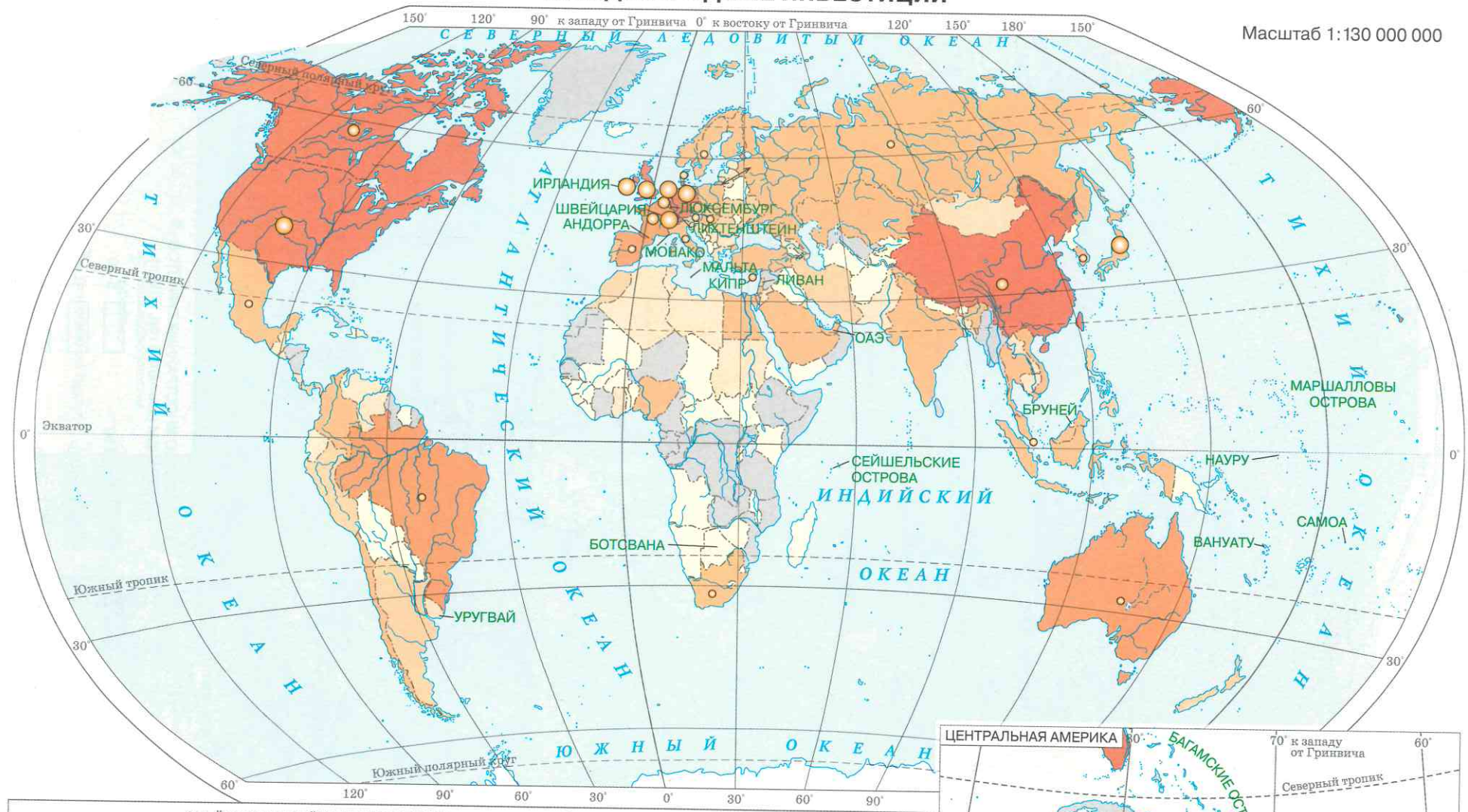

ОБЪЁМ ПРИВЛЕЧЁННЫХ ИНОСТРАННЫХ ИНВЕСТИЦИЙ (2019 г., млрд долл. США)

- более 1000
- 500–1000
- 100–500
- 50–100
- 10–50
- менее 10
- нет данных

СТРАНЫ-ЛИДЕРЫ ПО ОБЪЁМУ ИНВЕСТИЦИЙ, ВЛОЖЕННЫХ ЗА РУБЕЖ (2019 г., млрд долл. США)

- более 1500
- 1000–1500
- 200–1000

АНТИГУА И БАРБУДА — Страны с льготным режимом налогообложения

МИРОВОЙ ТУРИЗМ

Масштаб 1:83 000 000

от Гринвича
90°
120°
150°
180°
150°
60°
30°
0°
30°
ВИТЫЙ ОКЕАН
ТИХИЙ ОКЕАН
ИНДИЙСКИЙ ОКЕАН
ОКЕАН
РОССИЙСКАЯ ФЕДЕРАЦИЯ
КАЗАХСТАН
МОНГОЛИЯ
КИТАЙ
ИНДИЯ
ИНДОНЕЗИЯ
АВСТРАЛИЯ
ЯПОНИЯ
САУДОВСКАЯ АРАВИЯ
ЭФИОПИЯ
КЕНИЯ
Енисей
Волга
Ино
Янцзы
Инд
Ганг
Мекка
Дубай
Лахор
Лхаса
Шаолинь
Шанхай
Гонконг (Сянган)
Хюэ
Ангкор
Паттайя
БАНГКОК
Пхукет
СИНГАПУР
о. Калимантан
о. Тайвань
о. Хайнань
Гавайские острова
Нан-Мадол
о. Новая Гвинея
о. Суматра
Боробудур
о. Ява
о. Бали
о. Шри-Ланка
Мальдивы
о. Сокотра
Лалибела
Момбаса
Сейшельские о-ва
о. Маврикий
о. Реюньон
о. Мадагаскар
Дурбан
Кэрнс
Большой Барьерный риф
о-ва Фиджи
Улуру
Золотой Берег
Австралийские Альпы
Сидней
Мельбурн
о-ва Новая Зеландия
Долина гейзеров
о. Сахалин
Курильские о-ва
Саппоро
Атамик
ТОКИО
Нагано
Киото
СЕУЛ
ПЕКИН
Великая Китайская Стена
Каракорум
Иссык-Куль
Самарканд
Туркестан
Хива
Бухара
Мерв
ТЕГЕРАН
Исфахан
Персеполис
Кербела
Петра
Хургада
Медина
Луксор
Абу-Симбел
Приэльбрусье
Сочи
БАКУ
Анталья
Иерусалим
Тобольск
Казань
Ярославль
Владимир
МОСКВА
Южный Урал
Боровое
Алтай
оз. Байкал
Санкт-Петербург
Кировск
Дели
Лумбини
Агра
Санчи
Калькутта
Лаган
Луанг-Пхабанг
Гоа
Филиппинские о-ва
Южный тропик
Экватор
ДОЛЯ ТУРИЗМА В ВВП
менее 5%
5–10%
10–15%
15–20%
20–30%
более 30%
Масштаб 1:300 000 000
ТИЧЕСКИЕ ОБЪЕКТЫ
Центры игорного туризма
Районы приморского туризма
Курорты на побережьях
Бальнеологические курорты
Горнолыжные курорты
Районы сафари

МИРОВОЙ ТРАНСПОРТ

Масштаб 1:83 000 000

ТРАНСПОРТНАЯ СЕТЬ МИРА
(тыс. км, 2017 г.)

СТРУКТУРА МИРОВОГО ГРУЗО- И ПАССАЖИРООБОРОТА
(%, 2017 г.)

ТРАНСПОРТА

- Железнодорожный
- Автомобильный
- Трубопроводный
- Морской
- Внутренний водный
- Воздушный

ПЕРВАЯ ДЕСЯТКА СТРАН ПО ТОННАЖУ МОРСКОГО ФЛОТА (млн регистровых тонн брутто, 2019 г.)

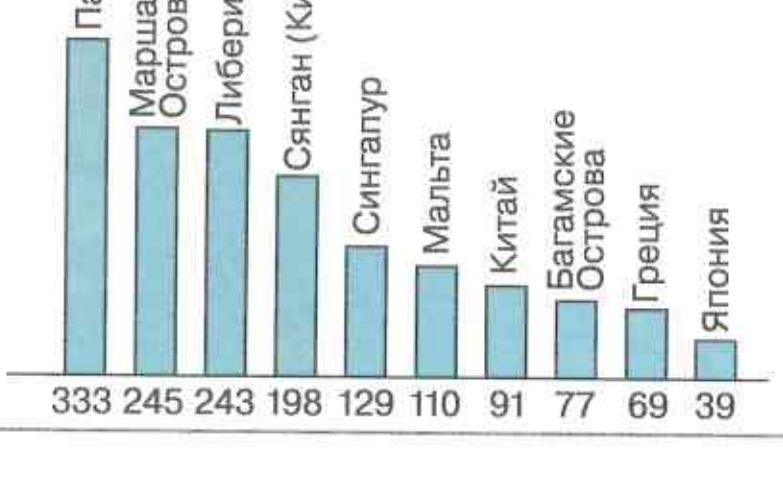

МОРСКИЕ ПОРТЫ

универсальные, нефтяные, угольные и рудные

с грузооборотом (млн т, 2016 г.)
- более 400
- от 200 до 400
- от 120 до 200
- от 60 до 120

Крупнейшие международные авиаузлы

Грузопотоки судоходных линий
- крупнейшие
- крупные
- значительные

Внутренние водные пути

6300 Расстояния (километры)

ОБЕСПЕЧЕННОСТЬ СЕТЬЮ ЖЕЛЕЗНЫХ И АВТОМОБИЛЬНЫХ ДОРОГ (км на 100 км^2 территории, 2020 г.)
- более 100
- от 25 до 100
- от 5 до 25
- менее 5

Важнейшие железные дороги

Скоростные железные дороги

Основные проливы Мирового океана
- I Гибралтарский
- II Ла-Манш
- III Скагеррак, Каттегат
- IV Босфор, Дарданеллы
- V Баб-эль-Мандебский
- VI Ормузский
- VII Малаккский
- VIII Зондский
- IX Макасарский
- X Берингов

ТРУБОПРОВОДНЫЙ ТРАНСПОРТ

Масштаб 1:130 000 000

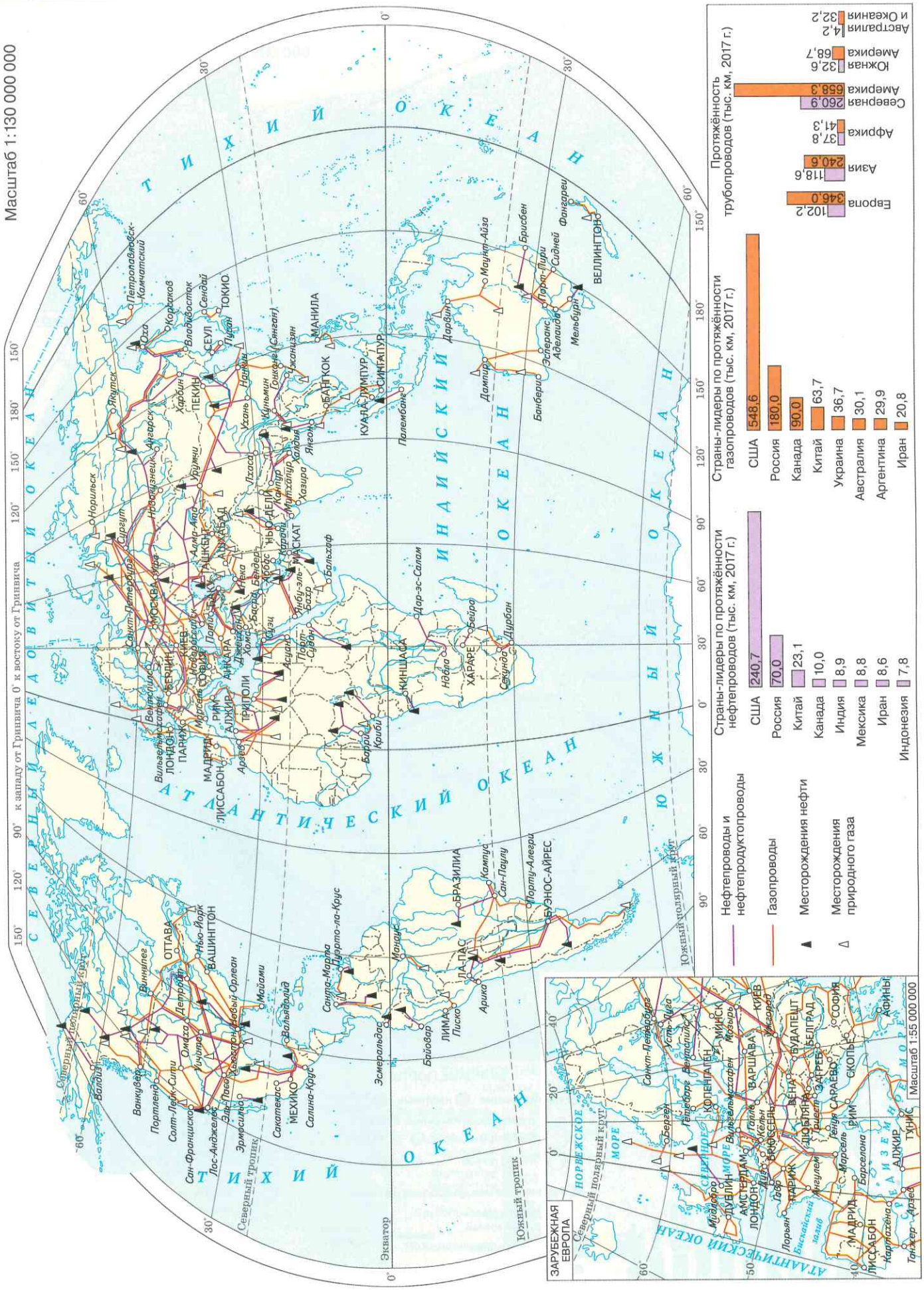

ВЕЛИКОБРИТАНИЯ

Масштаб 1:5 000 000

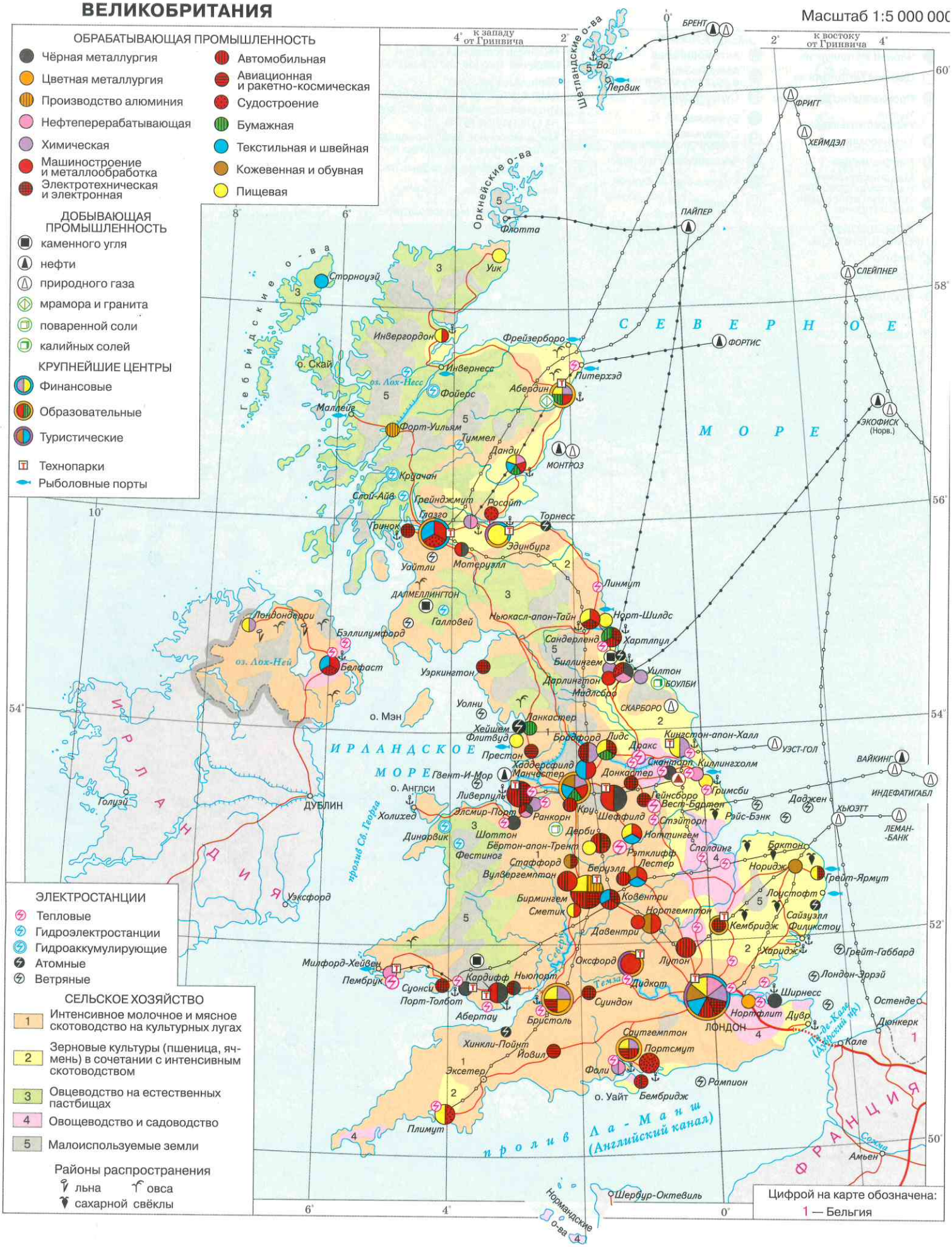

ФРАНЦИЯ

Масштаб 1:5 000 000

ГЕРМАНИЯ

Масштаб 1:3 700 000

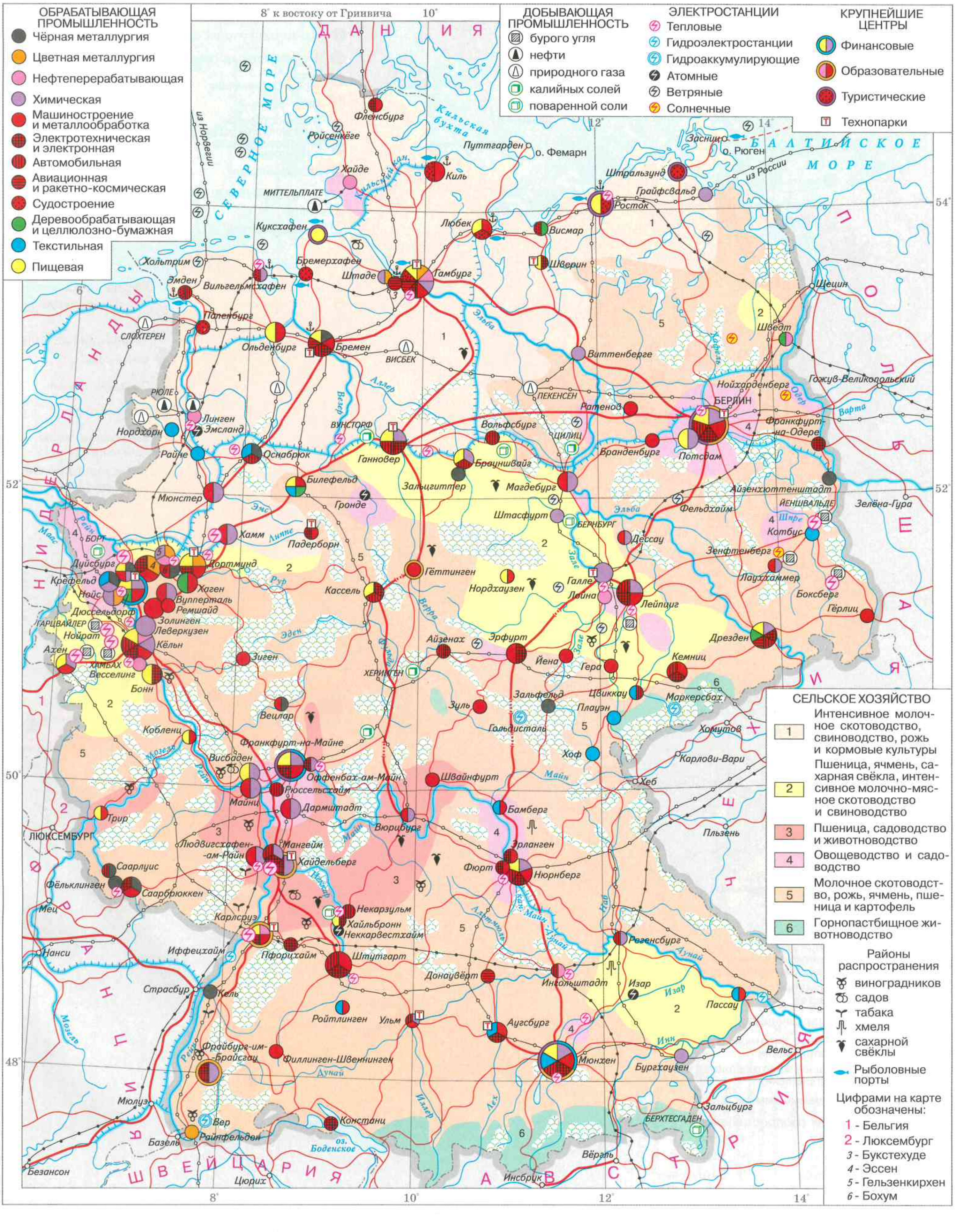

ИТАЛИЯ

Масштаб 1:5 000 000

КИТАЙ

Масштаб 1:20 000 000

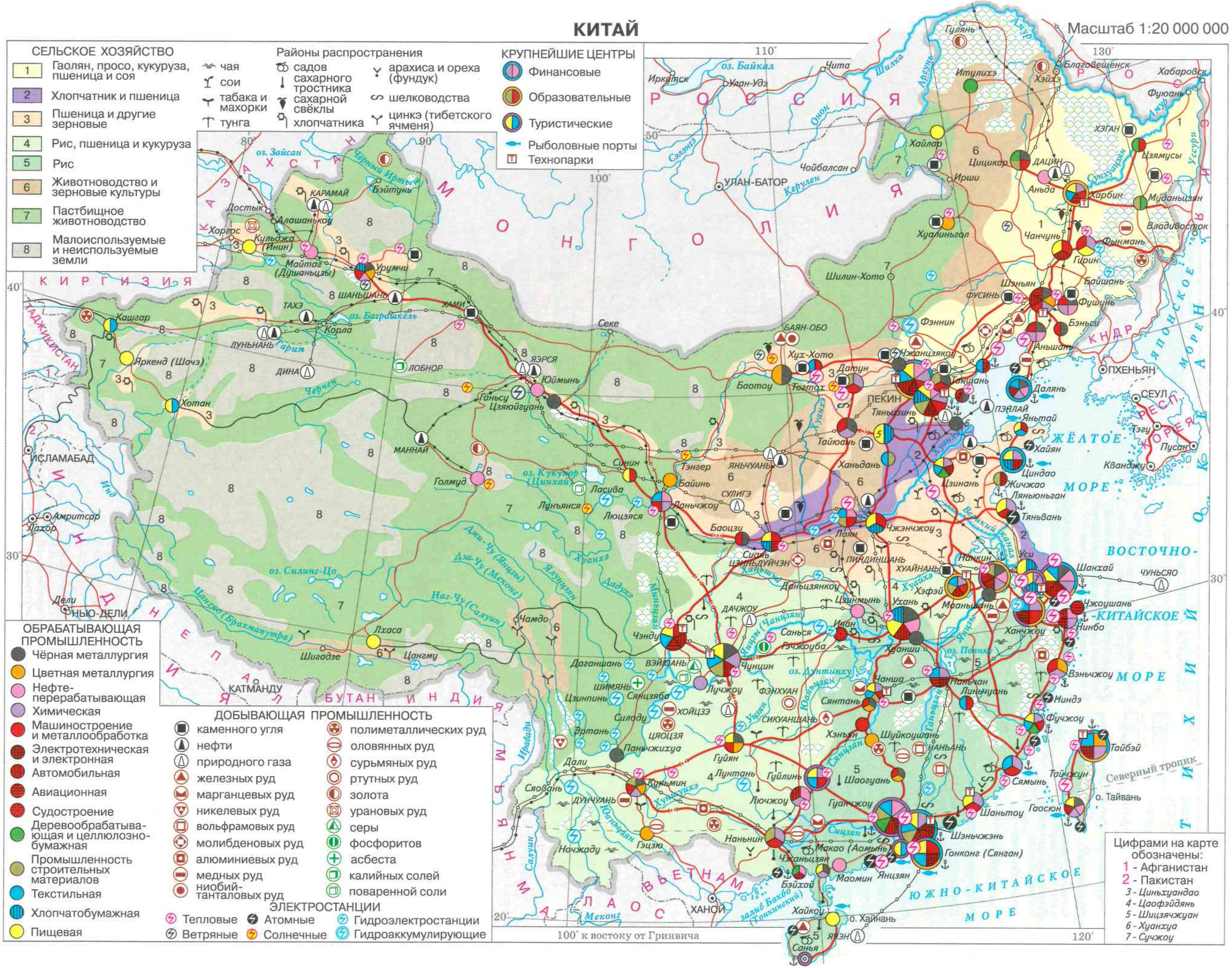

ЯПОНИЯ

Масштаб 1:8 000 000

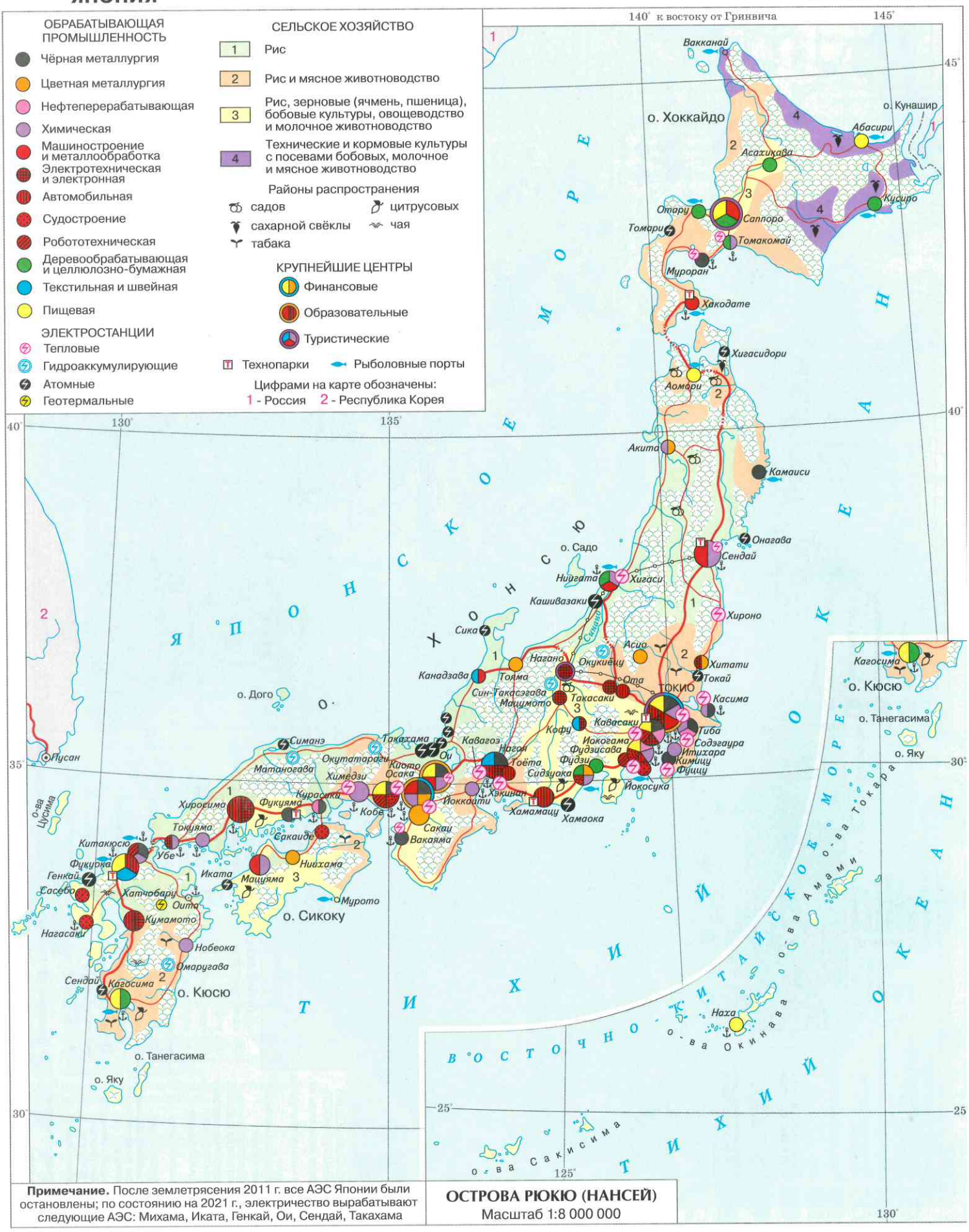

Примечание. После землетрясения 2011 г. все АЭС Японии были остановлены; по состоянию на 2021 г., электричество вырабатывают следующие АЭС: Михама, Иката, Генкай, Ои, Сендай, Такахама

ОСТРОВА РЮКЮ (НАНСЕЙ)
Масштаб 1:8 000 000

ИНДИЯ

Масштаб 1:17 000 000

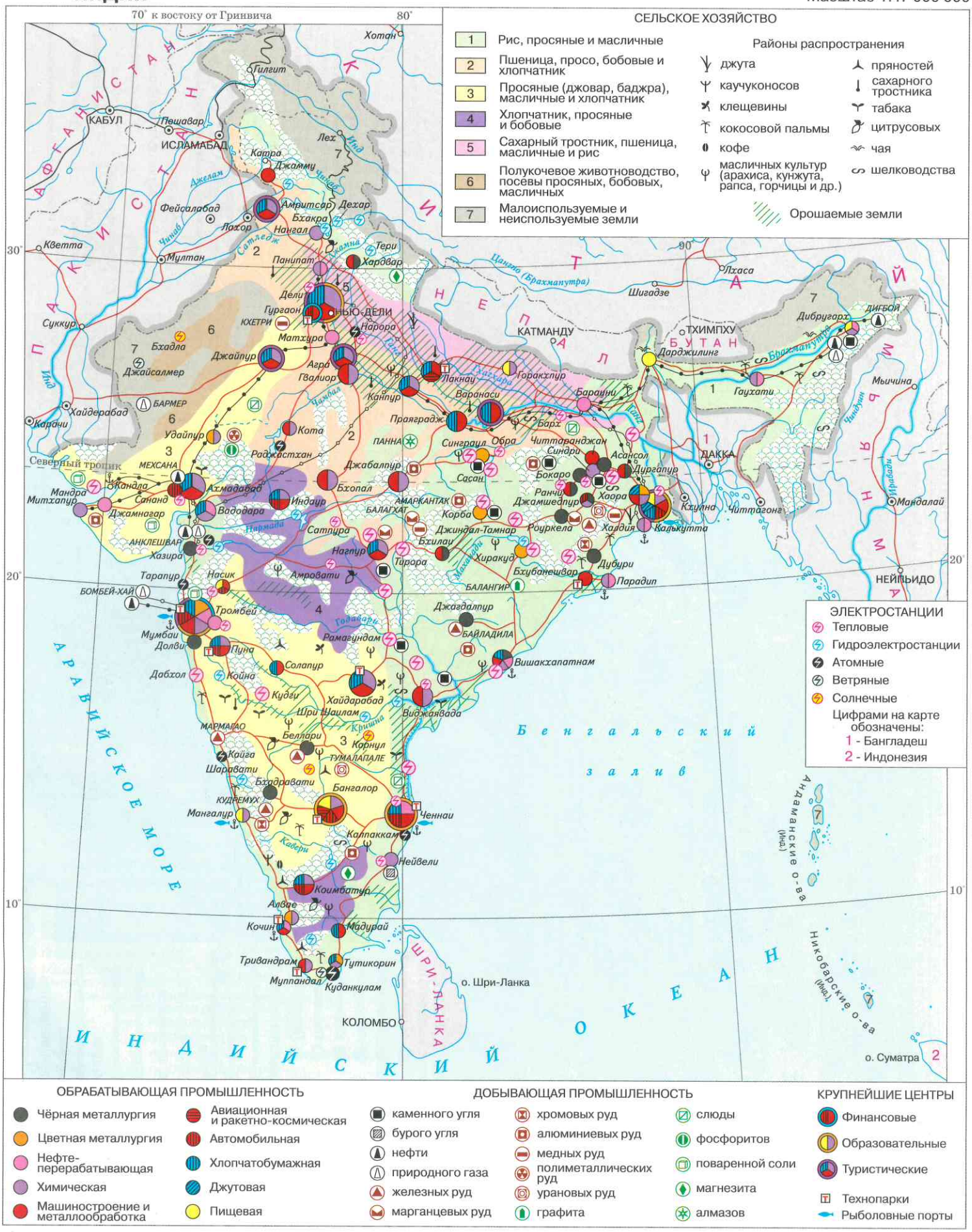

ЮГО-ЗАПАДНАЯ АЗИЯ

Масштаб 1:19 000 000

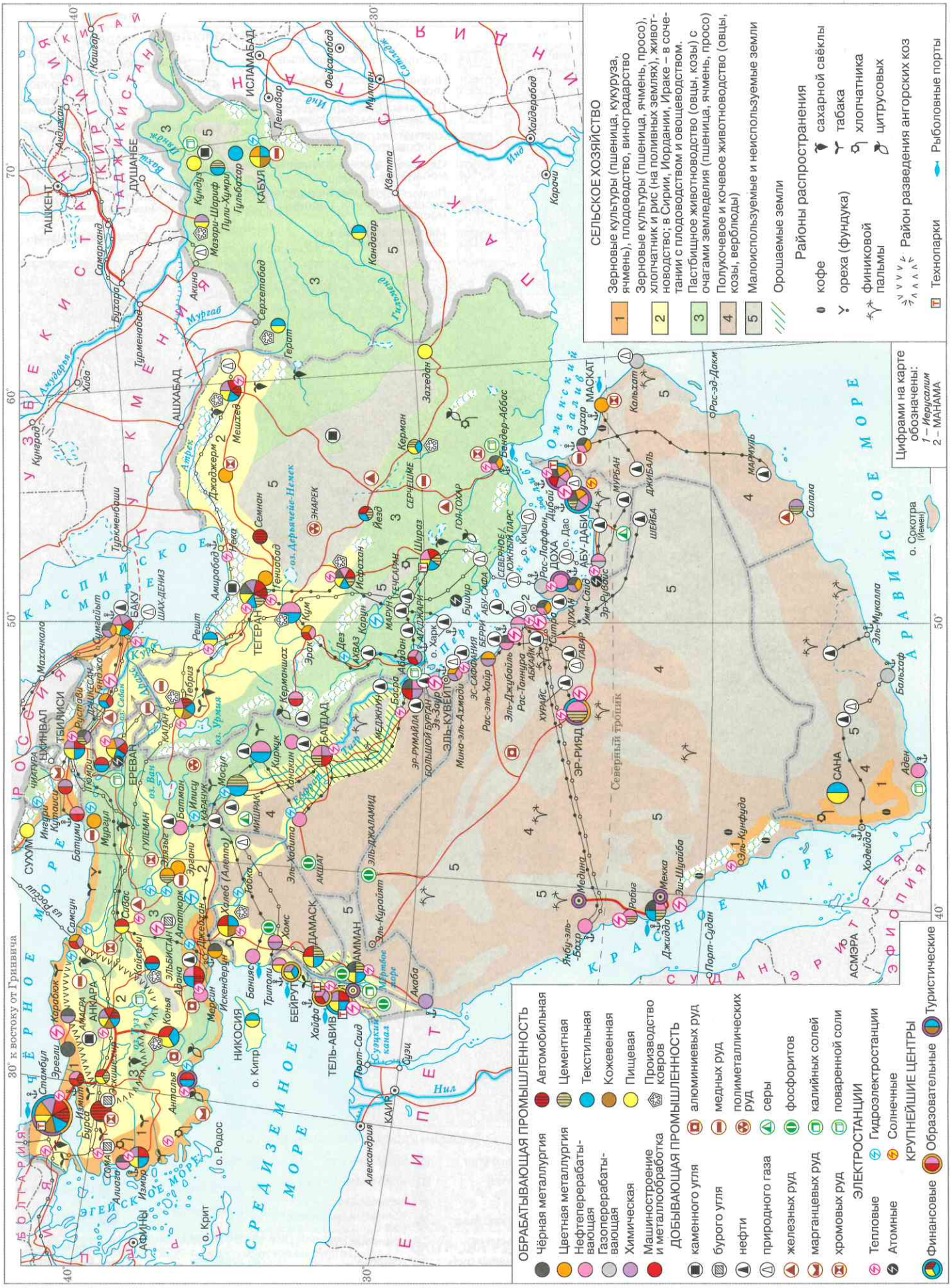

АФРИКА

Масштаб 1:42 000 000

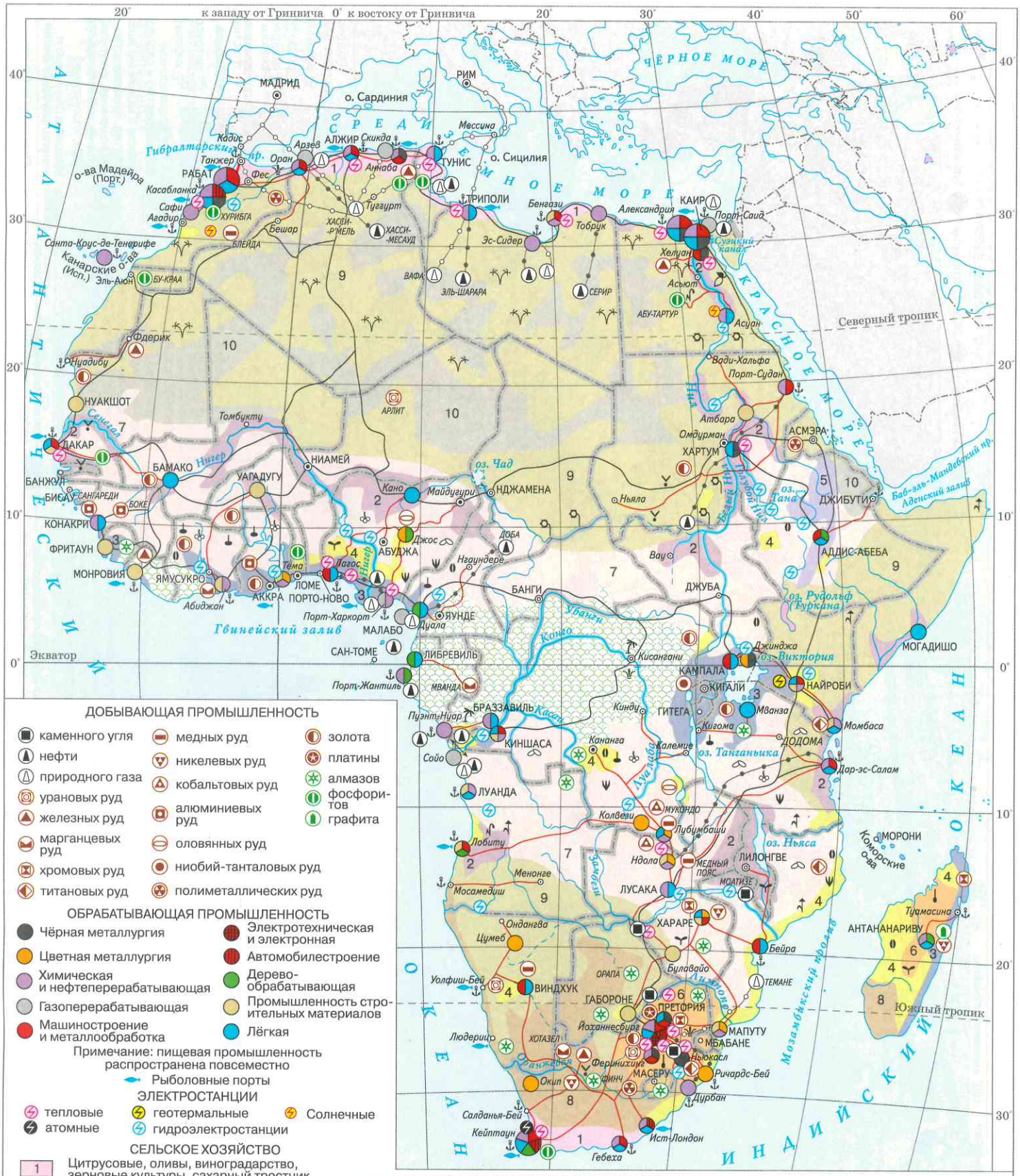

ДОБЫВАЮЩАЯ ПРОМЫШЛЕННОСТЬ

- каменного угля
- нефти
- природного газа
- урановых руд
- железных руд
- марганцевых руд
- хромовых руд
- титановых руд
- медных руд
- никелевых руд
- кобальтовых руд
- алюминиевых руд
- оловянных руд
- ниобий-танталовых руд
- полиметаллических руд
- золота
- платины
- алмазов
- фосфоритов
- графита

ОБРАБАТЫВАЮЩАЯ ПРОМЫШЛЕННОСТЬ

- Чёрная металлургия
- Цветная металлургия
- Химическая и нефтеперерабатывающая
- Газоперерабатывающая
- Машиностроение и металлообработка
- Электротехническая и электронная
- Автомобилестроение
- Дерево-обрабатывающая
- Промышленность строительных материалов
- Лёгкая

Примечание: пищевая промышленность распространена повсеместно

- Рыболовные порты

ЭЛЕКТРОСТАНЦИИ

- тепловые
- атомные
- геотермальные
- гидроэлектростанции
- Солнечные

СЕЛЬСКОЕ ХОЗЯЙСТВО

1. Цитрусовые, оливы, виноградарство, зерновые культуры, сахарный тростник
2. Хлопчатник, сахарный тростник, зерновые культуры
3. Кофе, какао, чай, сахарный тростник, арахис, кокосовая и масличная пальмы, зерновые культуры, корнеплоды
4. Зерновые культуры, хлопчатник, сахарный тростник, масличная пальма
5. Кофе, хлопчатник, просо
6. Пшеница, хлопчатник, плодовые культуры, животноводство
7. Пастбищное животноводство, зерновые культуры, арахис, хлопчатник
8. Овцеводство
9. Кочевое животноводство, оазисное земледелие
10. Малоиспользуемые и неиспользуемые земли

Районы распространения

- арахиса
- батата
- кофе
- маниока
- масличной пальмы
- проса и сорго
- риса
- сахарного тростника
- сизаля
- табака
- таро
- цитрусовых
- финиковой пальмы
- хлопчатника
- ямса

СОЕДИНЁННЫЕ ШТАТЫ АМЕРИКИ

Масштаб 1:19 000 000

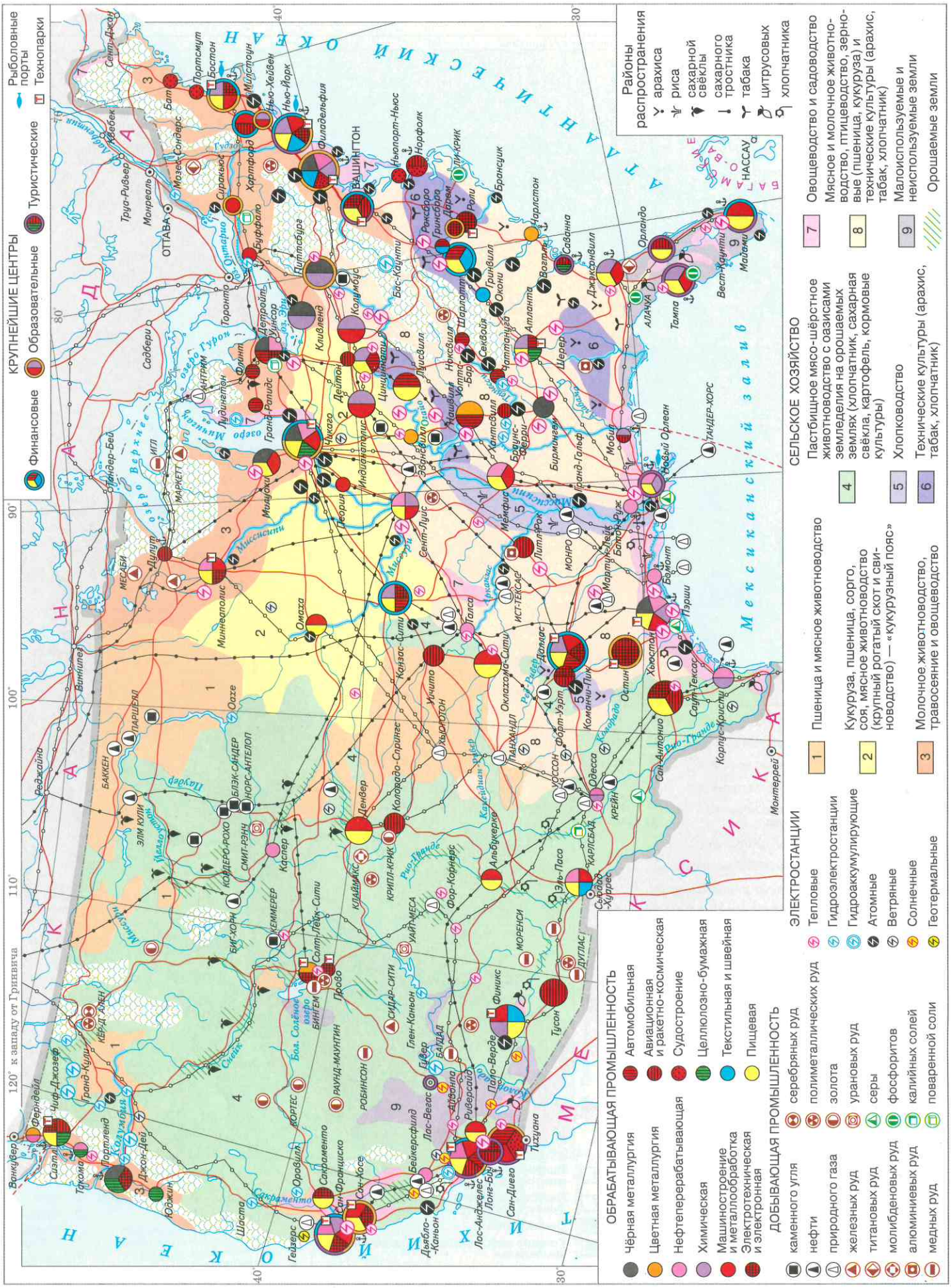

КАНАДА

Масштаб 1:25 000 000

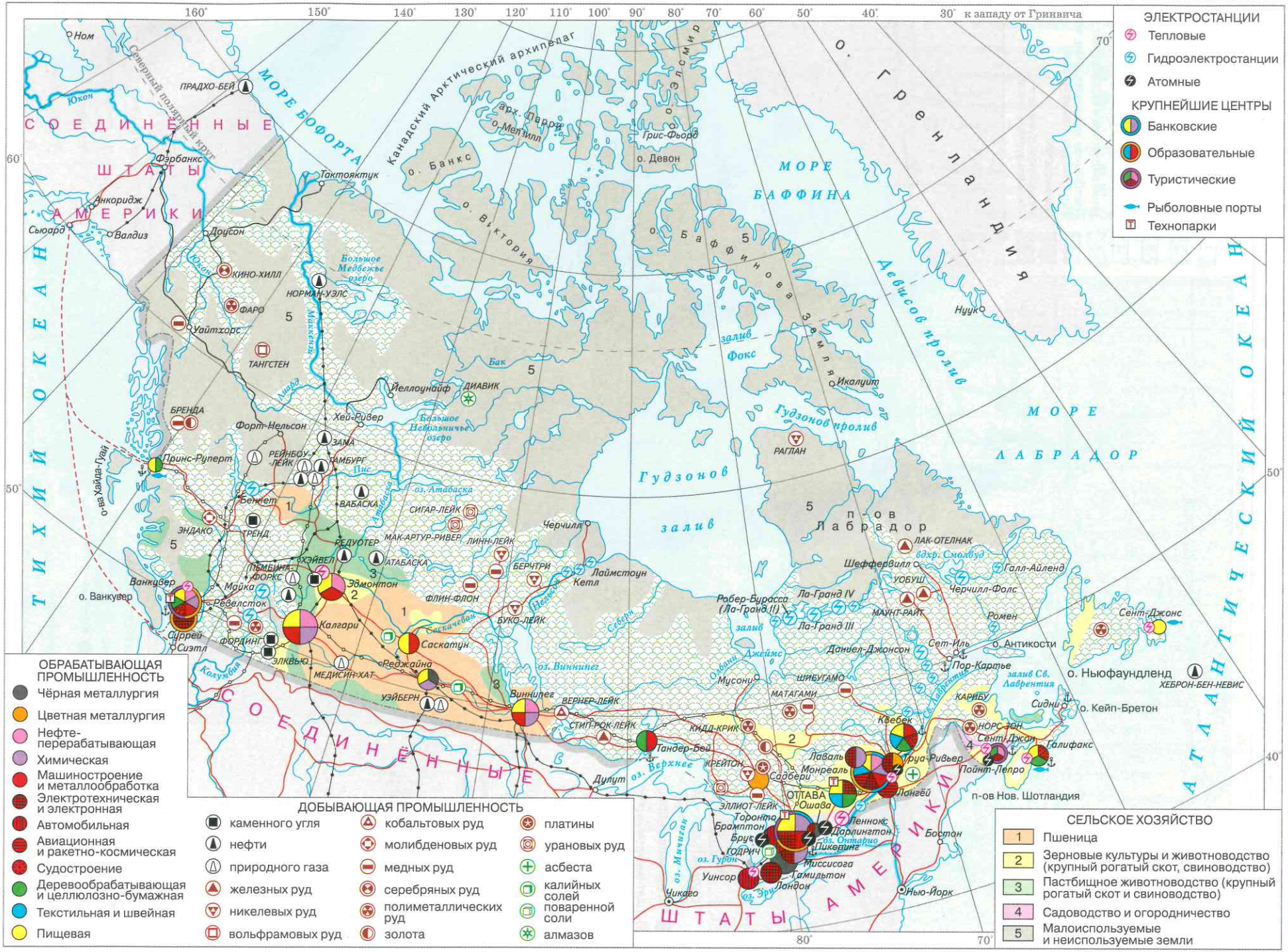

ЮЖНАЯ АМЕРИКА

Масштаб 1:42 000 000

АВСТРАЛИЯ

Масштаб 1:25 000 000

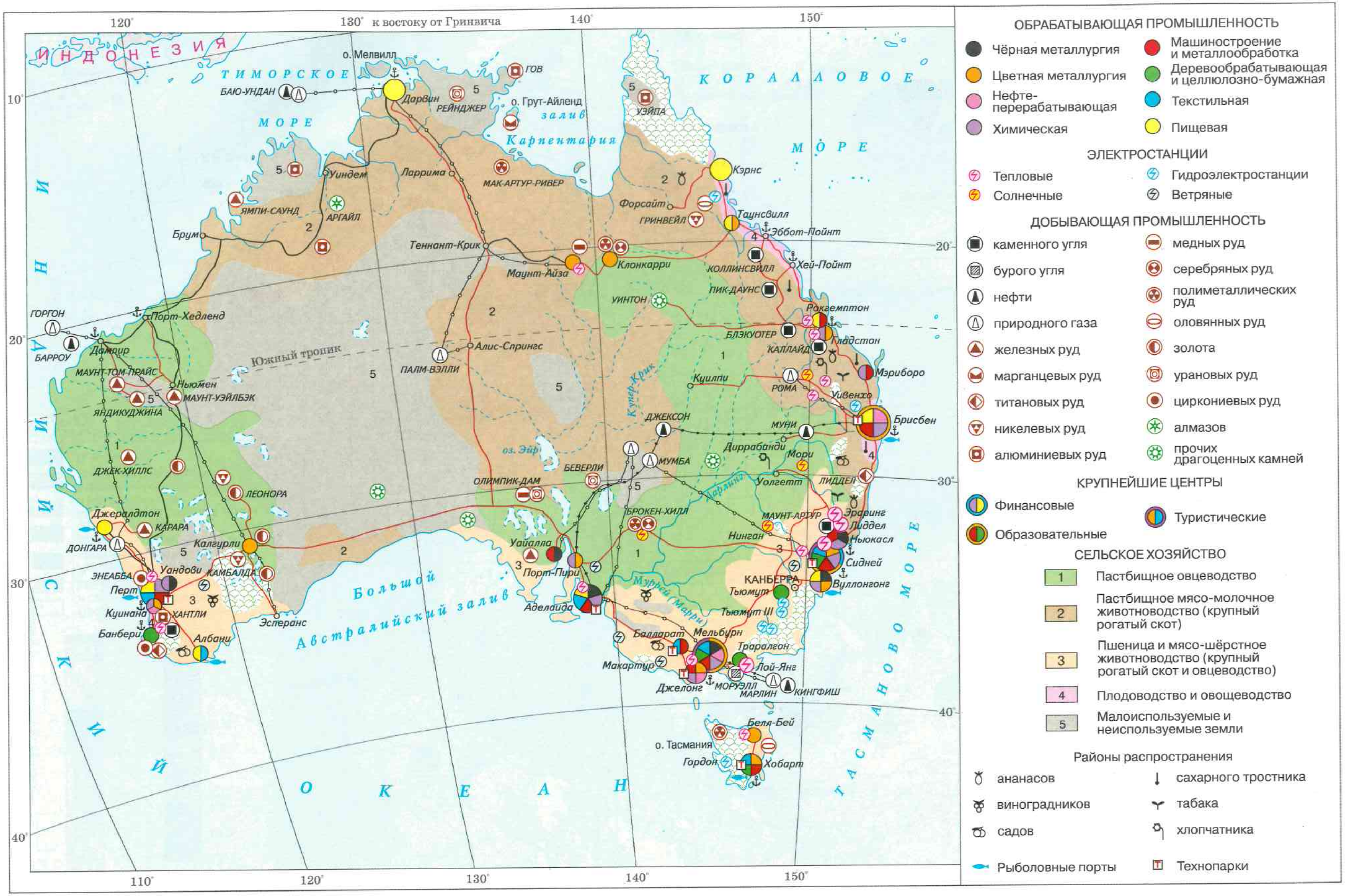

РОССИЯ В МИРЕ

Масштаб 1:150 000 000

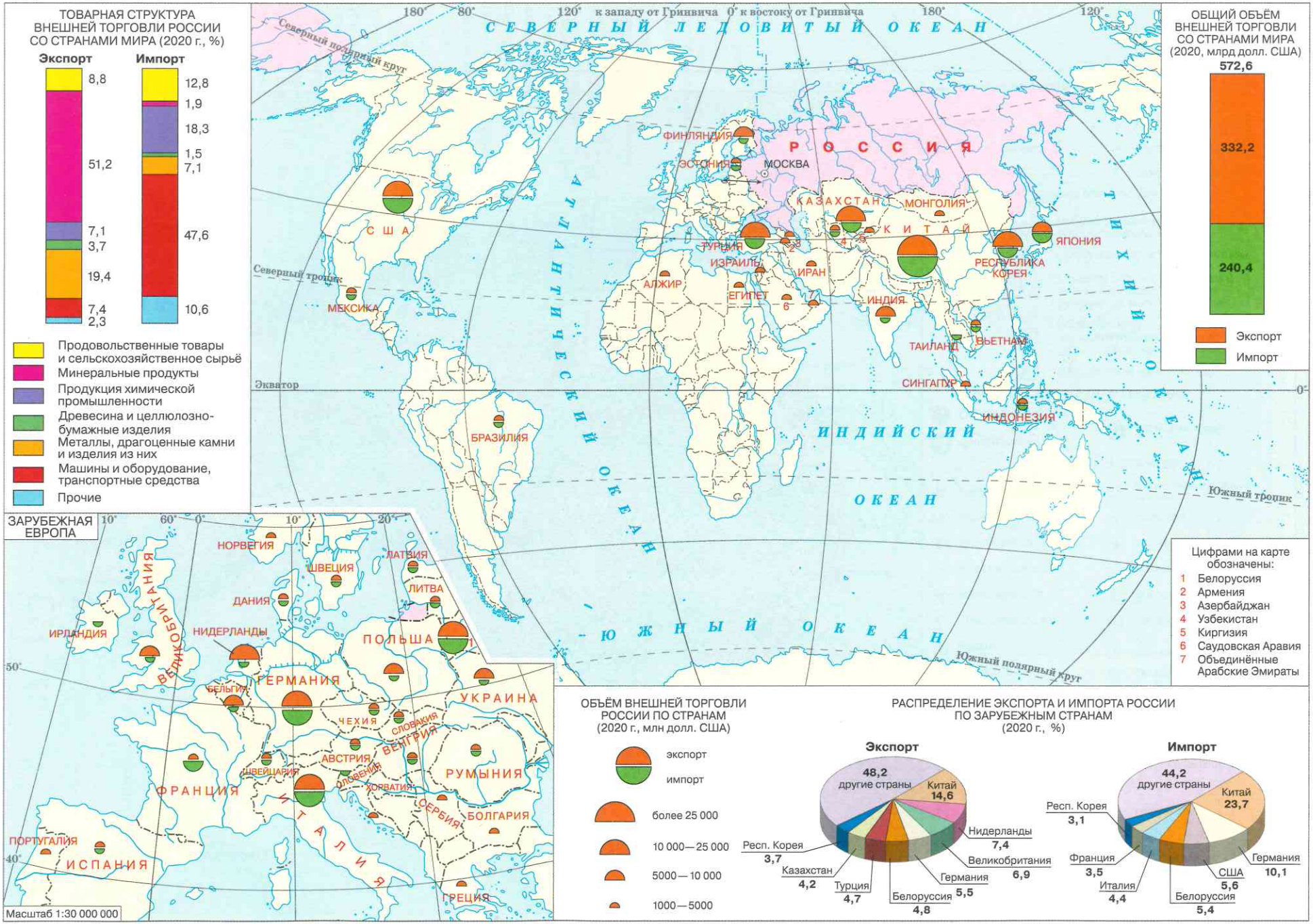

ГЛОБАЛЬНАЯ ПРОДОВОЛЬСТВЕННАЯ ПРОБЛЕМА

ПОТРЕБЛЕНИЕ КАЛОРИЙ

Масштаб 1:200 000 000

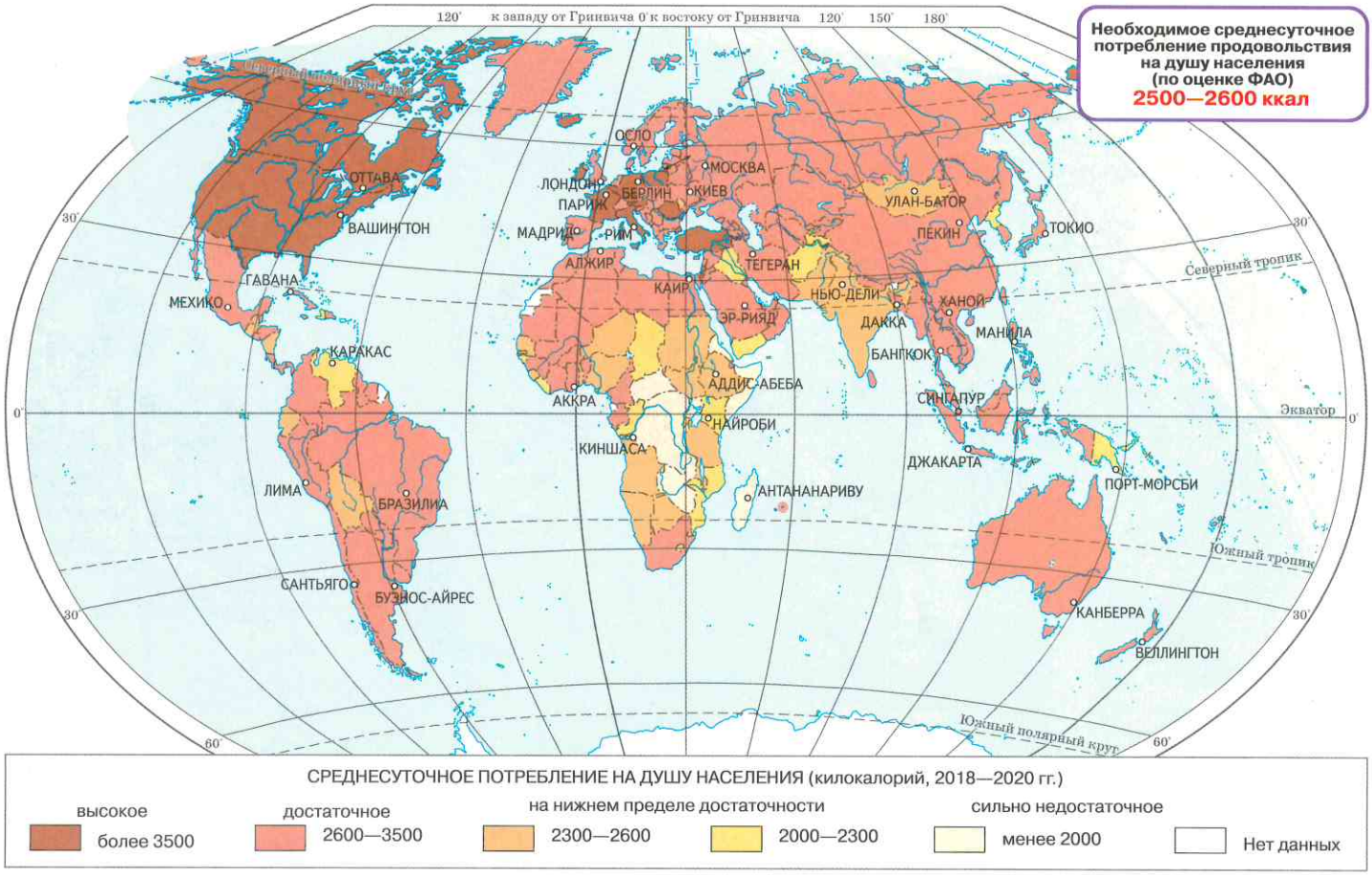

НЕДОЕДАНИЕ

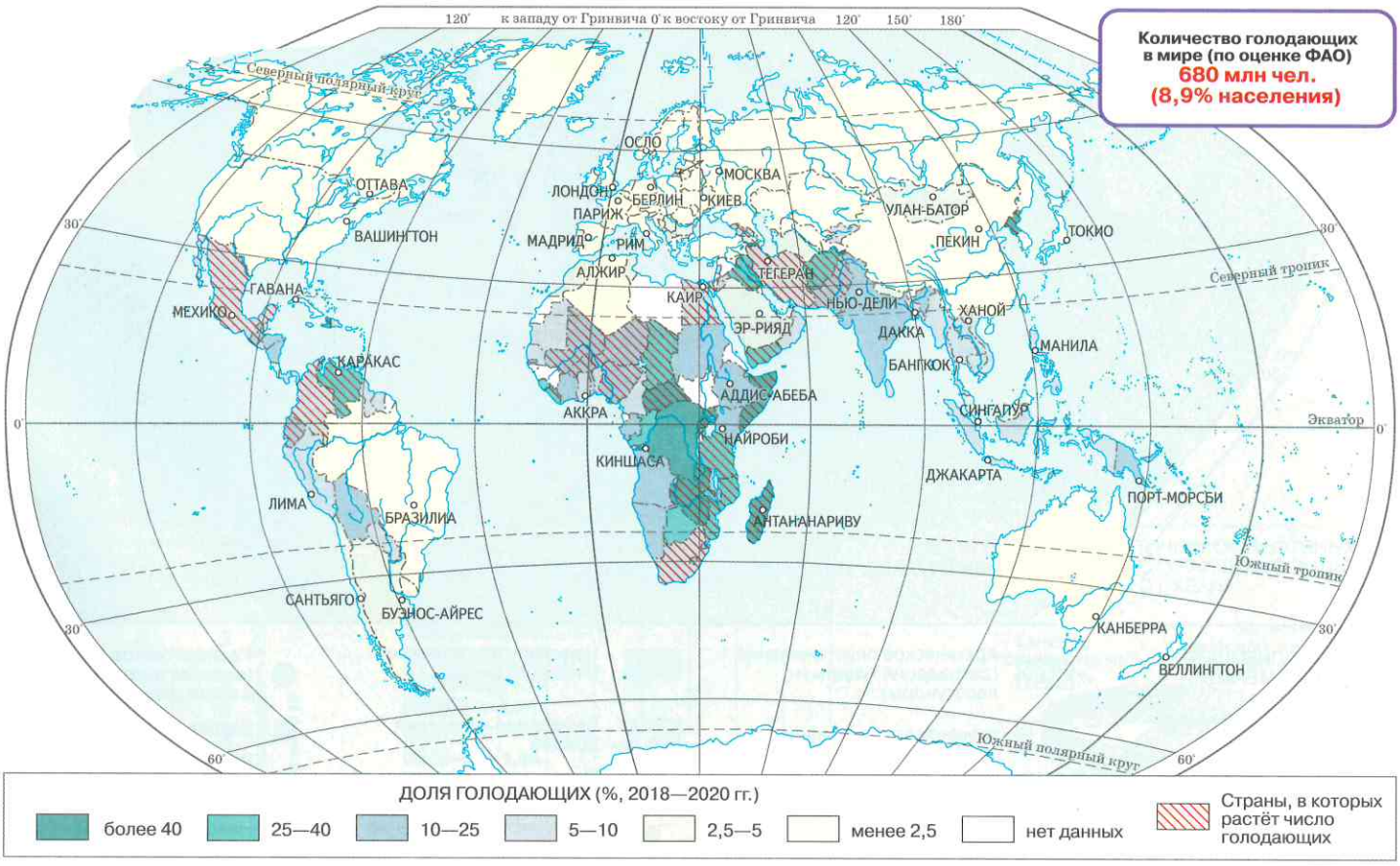

ЭКОЛОГИЧЕСКИЕ ПРОБЛЕМЫ МИРА

Масштаб 1:83 000 000

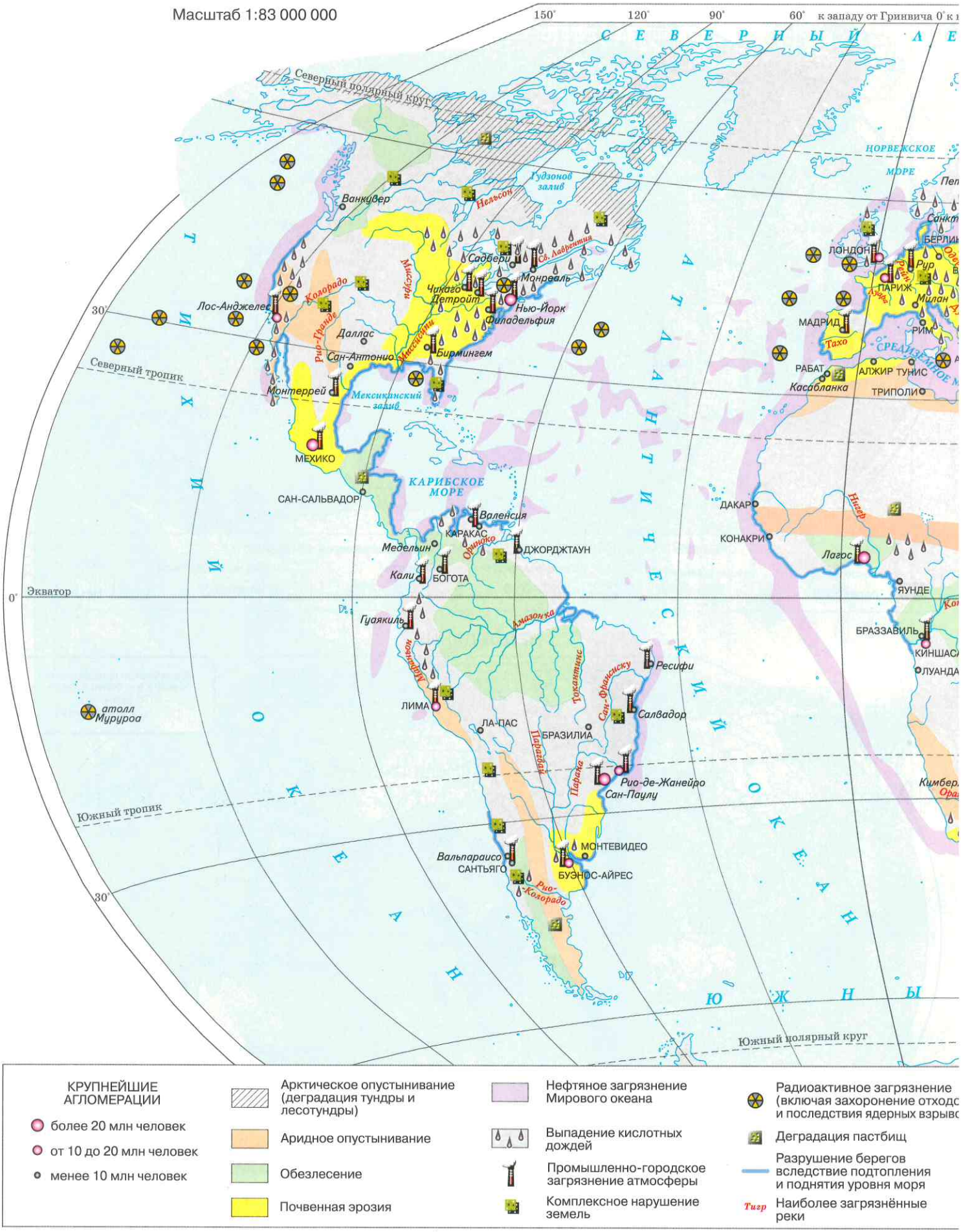

от Гринвича
90°
120°
150°
180°
150°
60°
30°
0°
30°
О В И Т Ы Й О К Е А Н
БАРЕНЦЕВО МОРЕ
КАРСКОЕ МОРЕ
МОРЕ ЛАПТЕВЫХ
ВОСТОЧНО-СИБИРСКОЕ МОРЕ
ЧУКОТСКОЕ МОРЕ
ОХОТСКОЕ МОРЕ
Норильск
Лена
Колыма
Индигирка
Енисей
Печора
Обь
Ангара
Череповец
Пермь
МОСКВА
Омск
Новокузнецк
Челябинск
Магнитогорск
Иртыш
Усть-Каменогорск
Дон
Волга
Урал
Мариуполь
Сырдарья
Амударья
ТАШКЕНТ
Стамбул
Аргунь
Амур
Харбин
Чанчунь
Шэньян
Баотоу
ПЕКИН
Тяньцзинь
СЕУЛ
ТОКИО
Осака
Сиань
Фукуока
Шанхай
Ханчжоу
Чэнду
Ухань
Чунцин
Янцзы
Сямынь
Хуанхэ
Тигр
Евфрат
ТЕГЕРАН
БАГДАД
КАИР
ЭЛЬ-КУВЕЙТ
Лахор
Брахмапутра
Ганг
Дели
ЭР-РИЯД
Карачи
ДАККА
Калькутта
Гуанчжоу
Гонконг (Сянган)
Тайбэй
ХАНОЙ
Меконг
МАНИЛА
АРАВИЙСКОЕ МОРЕ
ХАРТУМ
Мумбаи
Хайдарабад
Бенгальский залив
БАНГКОК
Бангалор
Ченнаи
Хошимин
АДДИС-АБЕБА
атолл Бикини
СИНГАПУР
о. Науру
ДЖАКАРТА
И Н Д И Й С К И Й
АНТАНАНАРИВУ
Маунт-Айза
о. Новая Каледония
Иоханнесбург
О К Е А Н
Перт
Брисбен
Сидней
Мельбурн
О К Е А Н

СТРАНЫ С МАКСИМАЛЬНЫМИ ВЫБРОСАМИ CO_2 (млн т, 2018 г.)
Китай 10 060
США 5410
Индия 2650
Россия 1710
Япония 1160
Германия 750
Иран 720
Республика Корея 650
Саудовская Аравия 620
Индонезия 610

СТРАНЫ-ЛИДЕРЫ ПО ПЛОЩАДИ ЛЕСОВ
Россия 20,4%
Бразилия 12,4%
Канада 8,7%
США 7,7%
Китай 5,5%
Австралия 3,3%
Дем. Респ. Конго 3,1%
Индонезия 2,3%
Перу 1,8%
Индия 1,8%
Указана доля стран в мировой площади лесов (%, 2020 г.)
млн га
0
100
200
300
400
500
600
700
800
900

ДОЛЯ РАЗЛИЧНЫХ ИСТОЧНИКОВ НЕФТЯНЫХ УГЛЕВОДОРОДОВ, ПОСТУПАЮЩИХ В ВОДЫ МИРОВОГО ОКЕАНА
Бытовые и промышленные воды 30%
Загрязнение нефтепродуктами при морских перевозках 27%
Атмосферные осадки 7%
Аварии нефтепроводов 12%
Со дна океанов 24%

ИНТЕГРАЦИОННЫЕ ОБЪЕДИНЕНИЯ

Масштаб 1:130 000 000

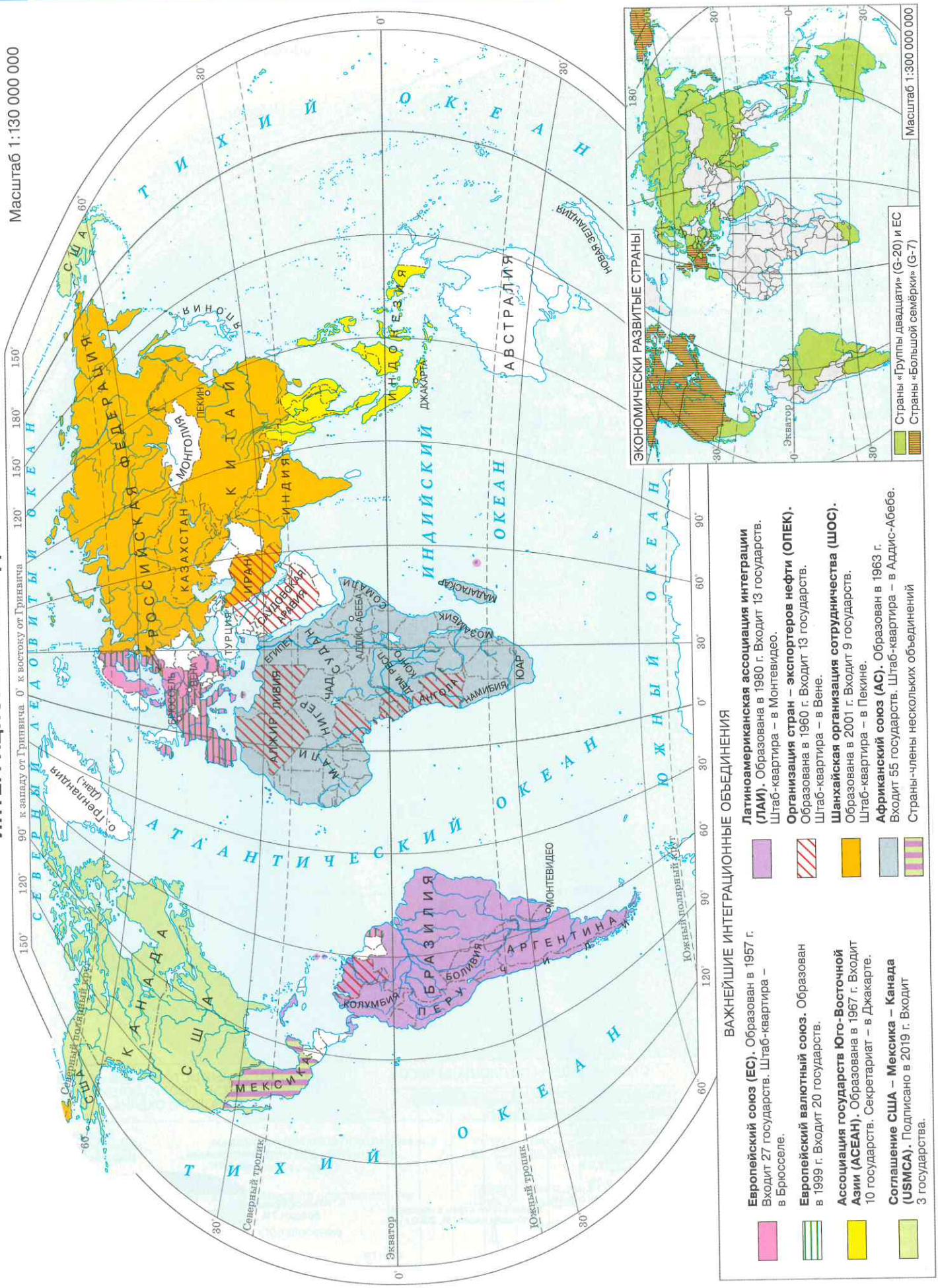

УСЛОВНЫЕ ЗНАКИ

ГОСУДАРСТВА И ТЕРРИТОРИИ

На политической карте мира

КИТАЙ — Государства

Америк. Самоа (США) — Владения

Майотта[3] — Территории с особым статусом

(Фр.) (Фр. Полинезия) — Принадлежность территорий (в том числе островов), входящих в состав государств и владений

НАСЕЛЁННЫЕ ПУНКТЫ

На политической карте мира

ВЕНА — Столицы государств

Кайенна — Центры владений и территорий с особым статусом

Калькутта — Прочие населённые пункты

- более 1 000 000 жителей
- от 500 000 до 1 000 000 жителей
- от 100 000 до 500 000 жителей
- менее 100 000 жителей

На экономических картах государств

ПАРИЖ — Столицы государств

Усань — Прочие населённые пункты

АРГАЙЛ — Месторождения полезных ископаемых

ГРАНИЦЫ

государственные

полярных владений Российской Федерации

Демаркационная линия между КНДР и Республикой Корея и между Индией и Пакистаном в Кашмире (северная часть Кашмира находится под контролем Пакистана)

ПУТИ СООБЩЕНИЯ

Железные дороги

Скоростные железные дороги

Железнодорожные туннели

Морские железнодорожные паромные переправы

Главные автомобильные дороги

Нефтепроводы

Газопроводы

Судоходные участки рек

Судоходные каналы

Морские порты

Леса

Примечания. 1. Специальное содержание карт уточнено на 2017–2021 годы с использованием данных ООН, Всемирного Банка и международной статистики, публикуемой Росстатом.
2. На экономических картах государств размер кружков промышленных центров отражает численность населения, размер знаков электростанций — их мощность.

Политическое устройство мира отражено на картах по состоянию на октябрь 2022 г.

УДК 373.167.1:911(084.4)
ББК 65.04(О)я6
Г35

12+

Учебное издание

ГЕОГРАФИЯ
10–11 классы
Атлас

Атлас составлен и подготовлен к изданию АО «Издательство «Просвещение»

Редактор к. г. н. *А. Н. Приваловский*
Картограф *Е. Г. Волкова*
Компьютерная вёрстка *Е. Г. Волкова*
Технический редактор *А. А. Боровикова*
Корректор *И. В. Андрианова*
Оформление обложки *Т. А. Гущина*

Подписано к печати 17.02.2023. Формат 60×90/8. Гарнитура «Прагматика».
Усл. печ. л. 6,0. Тираж 9500 экз.
Заказ № 26417 ЛДП.

Отпечатано в типографии ООО «ЛД-ПРИНТ», 196643, Россия, г. Санкт-Петербург, п. Сапёрный, ш. Петрозаводское, д. 61, стр. 6, тел. (812) 462-83-83, e-mail: office@ldprint.ru

Акционерное общество «Издательство «Просвещение».
Российская Федерация, 127473, г. Москва, ул. Краснопролетарская, д. 16, стр. 3, этаж 4, помещение I.
Адрес электронной почты «Горячей линии» — **vopros@prosv.ru**

ISBN 978-5-09-107363-8

© Картографическая основа. Росреестр, 2014
© АО «Издательство «Просвещение», 2021
© Художественное оформление.
АО «Издательство «Просвещение», 2021
Все права защищены

география

10-11 классы

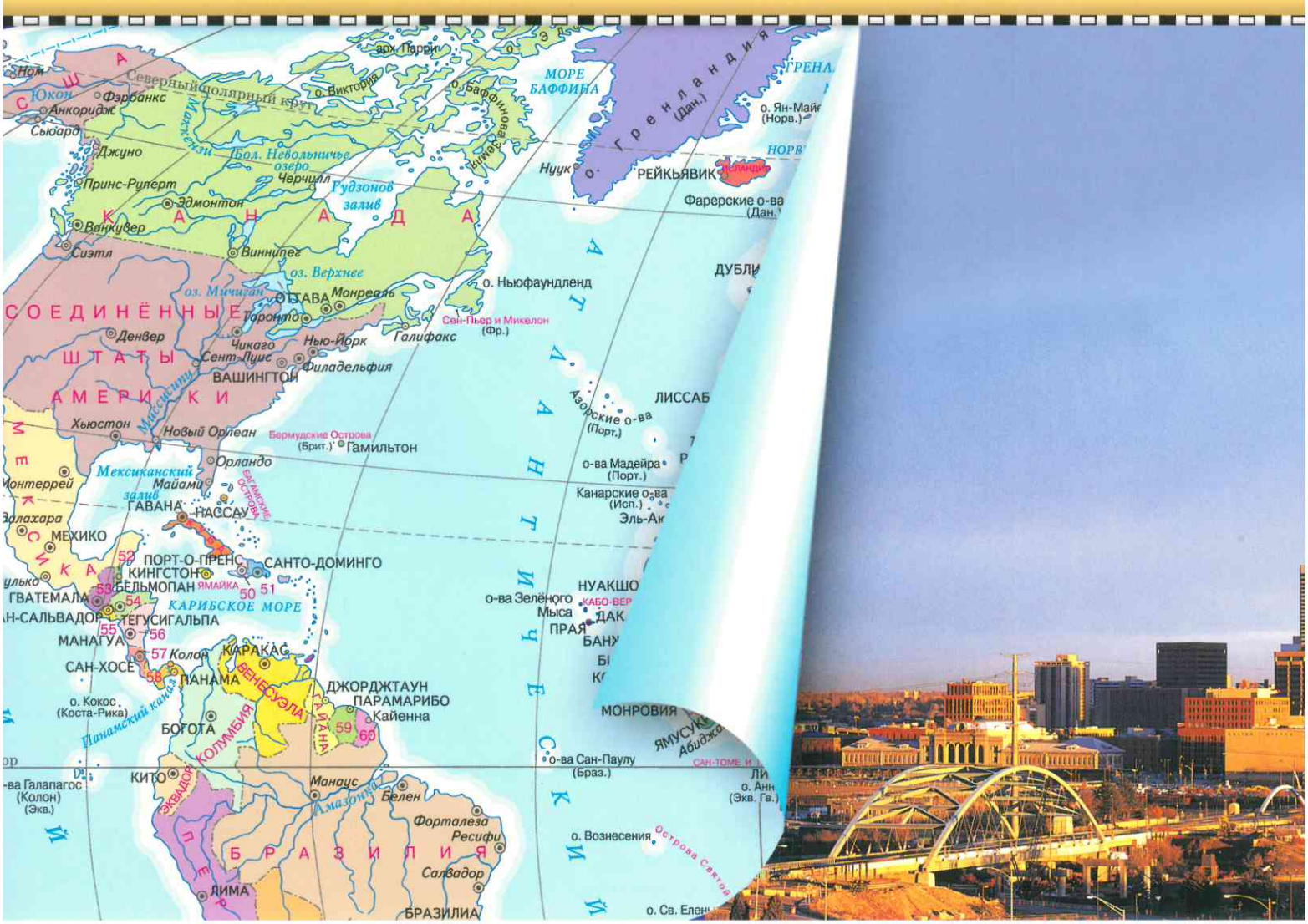

Официальный интернет-магазин издательства «Просвещение» **shop.prosv.ru**

12+

ISBN 978-5-09-107363-8

9 785091 073638

ПРОСВЕЩЕНИЕ
ИЗДАТЕЛЬСТВО
www.prosv.ru